Favela do Bode, bairro Pina, Recife (PE) – Foto: Leandro Vaz – Ministério das Cidades (2023)

DÉFICIT HABITACIONAL NO BRASIL 2023

FUNDAÇÃO JOÃO PINHEIRO

MINISTÉRIO DAS CIDADES

GOVERNO FEDERAL BRASIL UNIÃO E RECONSTRUÇÃO

GOVERNO DO ESTADO DE MINAS GERAIS

Governador
Romeu Zema Neto
Vice-Governador
Mateus Simões

SECRETARIA DE ESTADO DE PLANEJAMENTO E GESTÃO

Secretária de Estado de Planejamento e Gestão
Silvia Caroline Listgarten Dias

FUNDAÇÃO JOÃO PINHEIRO

Presidente
Luciana Lopes Nominato Braga
Vice-Presidente
Mônica Moreira Esteves Bernardi
Diretoria de Estatística e Informações (Direi)
Cláudio Djissey Shikida (Diretor)
Tomaz Duarte Moreira (Coordenador-Geral)
Vanessa Batista Borges de Carvalho
Coordenação de Editoração
Ana Paula da Silva

INSTITUIÇÃO CONTRATANTE

MINISTÉRIO DAS CIDADES
Jader Fontenelle Barbalho Filho

SECRETÁRIO NACIONAL DE HABITAÇÃO
Augusto Henrique Alves Rabelo

Chefe de Gabinete
Fabrício de Andrade Lebeis

Diretor do Departamento de Planejamento e Política Nacional de Habitação
Daniel Sigelmann

Coordenador – Geral de Planejamento
Hugo Leandro Gomes Gonçalves

Coordenadora – Geral de Política Nacional de Habitação
Nilza Emy Yamasaki

Equipe técnica
Frederico Queiroz Santos Pinto
Joseane Rotatori Couri
Nelson Carpes Neiva
Rhaiana Bandeira Santana

SECRETÁRIO NACIONAL DE PERIFERIAS
Guilherme Simões Pereira

Chefe de Gabinete
Vítor Araripe Freire Pacheco

Diretor do Departamento de Regularização, Urbanização Integrada e Qualificação de Territórios Periféricos
Flávio Tavares Brasileiro

Coordenadora – Geral de Articulação e Planejamento
Luana Alves de Melo

Coordenador – Geral de Urbanização
Henrique Soares Rabelo Adriano

Coordenador – Geral de Regularização Fundiária
Samuel da Silva Cardoso

Equipe técnica
Endyra de Oliveira Russo
Isis Bezerra Cavalcanti
Marina Amorim Cavalcanti de Oliveira
Wallace Rodrigues dos Santos

FUNDAÇÃO JOÃO PINHEIRO

DÉFICIT HABITACIONAL NO BRASIL 2023

Belo Horizonte

2025

FUNDAÇÃO JOÃO PINHEIRO

Alameda das Acácias, 70

São Luiz

Belo Horizonte – MG

CEP 31.275-150

Telefones: (31)3448-9711

E-mail: comunicação@fjp.mg.gov.br

Site: http://www.fjp.mg.gov.br

F981d Fundação João Pinheiro.
Déficit habitacional no Brasil 2023 / Fundação João Pinheiro. – Belo Horizonte, 2025.
76 p.: il.
Inclui bibliografia.

1. Habitação – Brasil – 2023. I. Título

CDU: 333.32 (81) “2023”

Elaborada por Ana Paula da Silva CRB- 6/2390

EQUIPE TÉCNICA

DIRETORIA DE ESTATÍSTICA E INFORMAÇÕES
Diretor
Cláudio Djissey Shikida

COORDENAÇÃO HABITAÇÃO E SANEAMENTO
Frederico Poley Martins Ferreira

ELABORAÇÃO
Arthur Morais Faasen
Blanca Valadares Ferreira
Cinthia Thimoteo Pinto
Francisco Humberto Bernardes de Oliveira
Frederico Poley Martins Ferreira
Gabriel do Carmo Lacerda
Júlia Rodrigues Gontijo
Mateus Ribeiro de Oliveira Gonçalves
Raquel de Mattos Viana

COORDENAÇÃO DE EDITORAÇÃO
Ana Paula da Silva
Ariane Machado
Graziella Napoli Terra Caldeira

LISTA DE ILUSTRAÇÕES

FIGURAS

Figura 1: Componentes e subcomponentes do déficit habitacional 10

GRÁFICOS

Gráfico 1: Distribuição do déficit habitacional por situação de domicílio, segundo regiões geográficas – Brasil – 2023 27
Gráfico 2: Composição relativa, por faixa de renda de salário mínimo domiciliar, do déficit habitacional, segundo regiões geográficas – Brasil – 2023 30
Gráfico 3: Composição relativa, por cor/raça do responsável, do déficit habitacional – Brasil – 2023 39
Gráfico 4: Ônus excessivo com aluguel urbano por arranjo domiciliar – famílias nucleares, unipessoais e outros (estendidos e compostos) – Brasil – 2023 56
Gráfico 5: Comparação do ônus excessivo com aluguel urbano relativo por arranjo domiciliar(1) – famílias nucleares, unipessoais e outros (estendidos e compostos) – Brasil – 2019, 2022 e 2023..... 57

MAPAS

Mapa 1: Déficit habitacional total por unidades da Federação – Brasil – 2023 18
Mapa 2: Principal componente do déficit habitacional por unidade da Federação – 2023..... 19
Mapa 3: Déficit habitacional relativo ao total de domicílios particulares ocupados (permanentes e improvisados) – unidades da Federação – 2023..... 20
Mapa 4: Déficit habitacional relativo ao total de domicílios particulares ocupados (permanentes e improvisados) por estrato geográfico do IBGE – 2023 22
Mapa 5: Principal componente do déficit habitacional por estrato geográfico do IBGE – 2023..... 23
Mapa 6: Proporção de domicílios com ônus e inadequação em relação ao total de domicílios com ônus excessivo com aluguel urbano, segundo unidades da Federação – Brasil – 2023..... 61
Mapa 7: Proporção de domicílios com ônus e inadequação de infraestrutura urbana em relação ao total de domicílios com ônus excessivo com aluguel urbano, segundo unidades da Federação – Brasil – 2023..... 65
Mapa 8: Proporção de domicílios com ônus e inadequação edilícia em relação ao total de domicílios com ônus excessivo com aluguel urbano, segundo unidades da Federação – Brasil – 2023 69

LISTA DE TABELAS

Tabela 1: Déficit habitacional por componente e total, segundo regiões geográficas, unidades da Federação e regiões metropolitanas – Brasil – 2023 15
Tabela 2: Composição do déficit habitacional por componente, segundo regiões geográficas, unidades da Federação e regiões metropolitanas (RM) – Brasil – 2023 24
Tabela 3: Déficit habitacional por situação de domicílio, segundo regiões geográficas, unidades da Federação e regiões metropolitanas (RMS) – Brasil – 2023 27
Tabela 4: Déficit habitacional, por faixa de renda de salário mínimo domiciliar, segundo regiões geográficas – Brasil – 2023 31
Tabela 5: Déficit habitacional, composição por faixa de renda de salário mínimo domiciliar, segundo regiões geográficas – Brasil – 2023 32
Tabela 6: Taxas específicas do déficit habitacional(1) por faixa de renda de salário mínimo domiciliar, por 1.000 domicílios particulares ocupados, segundo regiões geográficas – Brasil – 2023 34
Tabela 7: Déficit habitacional por sexo do responsável pelo domicílio, segundo regiões geográficas – Brasil – 2023 35
Tabela 8: Taxas específicas do déficit habitacional(1) por sexo do responsável pelo domicílio, por 1.000 domicílios particulares ocupados, segundo regiões geográficas – Brasil – 2023 36
Tabela 9: Déficit habitacional por cor/raça do responsável pelo domicílio, segundo regiões geográficas – Brasil – 2023 37
Tabela 10: Composição por cor/raça do responsável do déficit habitacional, segundo regiões geográficas – Brasil – 2023 40
Tabela 11: Taxas específicas do déficit habitacional(1) por raça/cor do(a) responsável pelo domicílio por 1.000 domicílios particulares ocupados, segundo regiões geográficas – Brasil – 2023 41
Tabela 12: Habitação precária por situação de domicílio, segundo regiões geográficas, unidades da Federação e regiões metropolitanas – Brasil – 2023 43
Tabela 13: Habitação precária por subcomponente, segundo regiões geográficas, unidades da Federação e regiões metropolitanas – Brasil – 2023 46
Tabela 14: Coabitação por situação de domicílio, segundo regiões geográficas, unidades da Federação e regiões metropolitanas – Brasil – 2023 49
Tabela 15: Coabitação por subcomponente, segundo regiões geográficas, unidades da Federação e regiões metropolitanas – Brasil – 2023 51
Tabela 16: Domicílios duráveis urbanos ocupados com ônus excessivo com aluguel urbano e inadequação, segundo regiões geográficas, unidades da Federação e regiões metropolitanas – Brasil – 2023 58
Tabela 17: Domicílios duráveis urbanos ocupados com inadequação de infraestrutura urbana e ônus excessivo com aluguel urbano, segundo regiões geográficas, unidades da Federação e regiões metropolitanas – Brasil – 2023 62
Tabela 18: Domicílios duráveis urbanos ocupados com inadequação edilícia e ônus excessivo com aluguel urbano, segundo regiões geográficas, unidades da Federação e regiões metropolitanas – Brasil – 2023 66

LISTA DE ABREVIATURAS E SIGLAS

FJP	Fundação João Pinheiro
IBGE	Instituto Brasileiro de Geografia e Estatística
PnadC	Pesquisa Nacional por Amostra de Domicílios Contínua
RM	Região Metropolitana
SM	Salário Mínimo
UF	Unidade Federativa

SUMÁRIO

1 INTRODUÇÃO 8

2 A QUESTÃO DOS DOMICÍLIOS IMPROVISADOS 12

3 DÉFICIT HABITACIONAL EM 2023 15

3.1 Déficit habitacional por situação (urbano e rural) 26

3.2 Déficit habitacional por faixa de renda de salário mínimo (SM) domiciliar 29

3.3 Déficit habitacional por sexo do responsável pelo domicílio 34

3.4 Déficit habitacional por cor/raça do responsável pelo domicílio 37

4 HABITAÇÃO PRECÁRIA 42

4.1 Habitação precária por situação (urbano e rural) 42

4.2 Subcomponentes da habitação precária: domicílios improvisados e domicílios rústicos 45

5 COABITAÇÃO 48

5.1 Coabitação por situação (urbano e rural) 48

5.2 Subcomponentes da coabitação: cômodos e unidade convivente déficit 51

6 ÔNUS EXCESSIVO COM O ALUGUEL URBANO 54

6.1 Ônus excessivo com o aluguel urbano por arranjo domiciliar 55

6.2 Domicílios em ônus excessivo com aluguel urbano e com alguma inadequação 57

6.2.1 Ônus excessivo com aluguel urbano e inadequação de infraestrutura urbana 62

6.2.2 Inadequação edilícia e ônus excessivo com aluguel urbano 65

7 CONSIDERAÇÕES FINAIS 70

REFERÊNCIAS 71

1 INTRODUÇÃO

Este relatório apresenta os resultados dos componentes e do indicador do déficit habitacional no Brasil para o ano de 2023.

A despeito das últimas alterações metodológicas (FJP, 2021), permanece a conceitualização — desde o primeiro relatório, em 1995 (FJP, 1995) — de que o déficit habitacional está relacionado à noção mais imediata e intuitiva do número de moradias necessárias para a solução de necessidades básicas habitacionais em determinado momento (FJP, 2017). Em outras palavras, o déficit habitacional estima a deficiência no estoque de moradias acumulada até determinado período de análise.

Mais detidamente, o déficit habitacional se relaciona, no primeiro nível, tanto com as deficiências do estoque de moradias quanto engloba as habitações sem condições de serem habitadas devido à precariedade dos materiais das paredes externas das habitações. Adicionalmente, o déficit habitacional também se vincula com a necessidade de acesso à habitação em função da coabitação familiar não desejada — por exemplo, famílias que pretendem constituir um domicílio unifamiliar e não conseguem. Por fim, capta também os domicílios de baixa renda alugados em áreas urbanas, cujo valor do aluguel acaba por comprometer o orçamento domiciliar no que se refere à satisfação de outras necessidades básicas.

Essas dimensões — que constituem os componentes do déficit habitacional — estão dispostas na Figura 1. Cada componente — habitação precária, coabitação e ônus excessivo com o aluguel urbano — envolve soluções e políticas específicas — por exemplo, por incremento de estoque, reposição, realocação, mudança de uso, aluguel social etc. Além disso, cada componente se manifesta no território segundo os diferentes padrões regionais, socioeconômicos, demográficos e culturais do Brasil.

Ressalta-se que a partir de 2016 (FJP, 2021), com a nova Pesquisa Nacional por Amostras de Domicílios Contínua (PnadC), foram necessários ajustes metodológicos que podem ser resumidos como:

a) o uso das informações do Cadastro Único (CadÚnico) para captar as informações acerca dos domicílios improvisados;

b) a necessidade de recomposição dos arranjos familiares para identificação da existência de núcleos secundários no domicílio e em situação de adensamento excessivo — as chamadas unidades domésticas conviventes em déficit.

Do ponto de vista operacional, o cálculo do déficit é feito de forma hierárquica: os componentes — e seus subcomponentes — são somados, descontando os domicílios identificados em cada componente anterior, com exceção das unidades domésticas conviventes, resultando no indicador geral de déficit habitacional. Assim, conforme a Figura 1, existem as seguintes etapas:

a) os domicílios particulares ocupados são a soma entre o total de domicílios particulares permanentes ocupados da PnadC 2023 e os domicílios particulares improvisados do CadÚnico 2023 (Apêndice A);

b) o cômputo dos domicílios improvisados, calculados a partir do CadÚnico 2023[1];

c) o cômputo dos domicílios rústicos, calculados a partir da PnadC 2023;

d) o cômputo dos domicílios cômodos, calculados a partir da PnadC 2023;

e) o cômputo dos domicílios ônus excessivo com o aluguel urbano, calculados a partir da PnadC 2023, considerando apenas os domicílios urbanos alugados, com renda domiciliar de até três salários mínimos (SM) e que gastem mais de 30% da sua renda com o aluguel;

f) o cômputo das unidades domésticas conviventes déficit, calculados a partir da PnadC 2023, que independe da existência de outro componente do déficit no domicílio.

Em síntese, com a soma dos subcomponentes de domicílios improvisados com os domicílios rústicos, tem-se a componente habitação precária. E com a soma dos subcomponentes de domicílios do tipo cômodo com as unidades domésticas conviventes déficit, tem-se a componente de coabitação. O indicador geral do déficit habitacional é a soma do total de domicílios em situação de habitação precária, coabitação e ônus excessivo com o aluguel urbano.

[1] Neste cálculo foram aplicados filtros de consistência e para os municípios com proporções extremas, por porte populacional e região de famílias em domicílios improvisados em relação ao total de domicílios particulares ocupados, foi elaborada uma metodologia de estimativa (FJP, 2025) discutida a seguir.

Figura 1: Componentes e subcomponentes do déficit habitacional

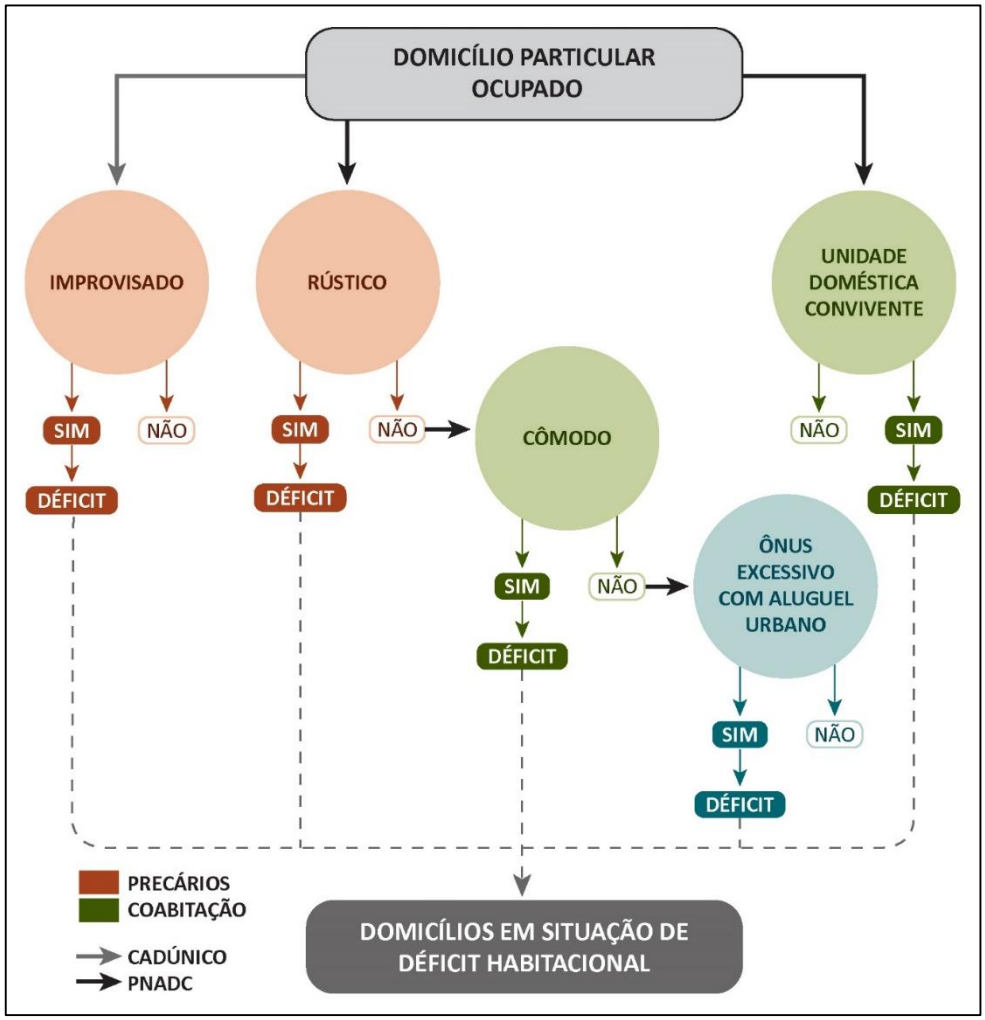

Fonte: Elaboração própria.

Dessa maneira, o presente relatório procura sumarizar os principais resultados do déficit habitacional e cumpre o intuito de oferecer um indicador, aos diversos níveis de governo e à sociedade, para potenciais intervenções nas habitações e no espaço urbano. Complementarmente, para acessar as informações mais desagregadas e para novos cruzamentos de variáveis — por exemplo, por sexo, cor/raça do responsável pelo domicílio e faixa de renda domiciliar—, estão disponíveis uma planilha e um painel no sítio eletrônico da Fundação João Pinheiro[2]. Também, para eventual aprofundamento e discussão metodológica, recomenda-se a leitura do relatório da Fundação João Pinheiro (2021).

[2] No sítio eletrônico da Fundação João Pinheiro estão disponíveis os estudos anuais referentes às necessidades habitacionais e a evolução dos indicadores desde 1995. Disponível em: https://fjp.mg.gov.br/deficit-habitacional-no-brasil/.

Especificamente, este relatório se divide em sete partes, além das referências e apêndice. A primeira parte refere-se a esta introdução. A segunda apresenta a metodologia de correção aplicada aos domicílios improvisados em 2023, subcomponente da habitação precária. A terceira apresenta os resultados para o indicador do déficit habitacional. A quarta, quinta e sexta partes especificam os resultados, respectivamente, para as habitações precárias, coabitação e ônus excessivo com o aluguel urbano. Mais especificamente, e como novidade, a sexta parte analisa os domicílios que estão em ônus excessivo com aluguel urbano e que também têm alguma inadequação. Essa discussão, ainda pouco levantada pela literatura, vem ganhando cada vez mais importância para se pensar nas políticas habitacionais. Por fim, na sétima e última parte, tece-se uma breve conclusão sobre os resultados estimados.

2 A QUESTÃO DOS DOMICÍLIOS IMPROVISADOS

Apesar da maioria das soluções metodológicas desenvolvidas para o cálculo do déficit habitacional de 2023 já constarem no relatório metodológico de déficit habitacional e de inadequação de domicílios a partir da PnadC de 2016 a 2019 (FJP, 2021), e de algumas outras importantes soluções metodológicas e discussões constarem nas notas técnicas (FJP, 2023, 2025), esta seção compila e procura aperfeiçoar algumas das principais questões que envolvem o subcomponente de domicílios improvisados, único subcomponente obtido a partir das informações do Cadastro Único para Programas Sociais (CadÚnico).

Como a PnadC não inclui informações sobre domicílios particulares improvisados, apenas particulares permanentes, desde 2016 a alternativa metodológica encontrada foi recorrer às informações do CadÚnico, devido à constância na atualização da base e ao nível de desagregação territorial das informações (FJP, 2021).

No entanto, além das diferenças entre as bases, especialmente sobre a unidade básica de análise, domicílios para PnadC e famílias para CadÚnico, desde novembro de 2021 observou-se um aumento expressivo no número de famílias unipessoais cadastradas no CadÚnico. FJP (2023) discute essa expansão dos unipessoais e exibe como o indicador habitacional de domicílios improvisados se mostrou sensível a esse fato. Isso resultou em um substancial aumento nas proporções de famílias unipessoais residindo em domicílios improvisados, em relação ao total de improvisados, para os anos de 2022 e 2023.

Por sua vez, soma-se à essa explosão dos unipessoais, a diferença conceitual de improvisados entre o Censo e o CadÚnico, que também contribui para sobrestimar as famílias em domicílios improvisados no CadÚnico — ver valores ilustrados em FJP (2025).

No Censo, domicílio improvisado é definido como:

> [...] aquele localizado em uma edificação que não tenha dependências destinadas exclusivamente a moradia (por exemplo, dentro de um bar), como também os locais inadequados para habitação e que, na data de referência, estavam ocupados por moradores (IBGE, 2010, p. 68).

Além do mais, é ressaltada a finalidade da edificação, que deve ser diferente de residencial.

No CadÚnico, domicílio improvisado é definido como:

> [...] espaço que, no momento da entrevista, está precariamente adaptado pela família para servir de moradia. Nesses domicílios, geralmente não é possível

> distinguir cômodos ou individualizar os espaços. Normalmente, não têm acesso a serviços básicos de abastecimento de água, energia elétrica, saneamento ou coleta de lixo, configurando uma situação de extrema vulnerabilidade (Brasil, 2023, p. 44).

Além do mais, é explicitado, no *Manual do Sistema de Cadastro Único*, que "quando houver dúvida entre Domicílio Particular Permanente e Domicílio Particular Improvisado, marque o Domicílio Particular Improvisado, para não deixar de registrar a vulnerabilidade da família" (Brasil, 2023, p. 51). Logo, o conceito de "improvisados" no CadÚnico é mais amplo, buscando captar, também, a vulnerabilidade habitacional da família.

Dessa forma, para as estimativas de famílias residentes em domicílios improvisados já em 2022 (FJP, 2024) procurou-se utilizar os dados do CadÚnico de 2021, excluindo da amostra as famílias unipessoais cadastradas a partir de novembro de 2021. No entanto, para as próximas estimativas, de 2023 em diante, as informações de 2021 ficariam desatualizadas e, por isso, adotou-se a metodologia de estimativa de famílias em domicílios improvisados conforme descrito na nota técnica (FJP, 2025). Ademais, ressalta-se, desde 2023, uma série de medidas para averiguação dos cadastrados, especialmente das famílias unipessoais[3], por parte do Governo Federal com o objetivo de qualificar os dados do CadÚnico[4].

A proposta é prosseguir com a utilização do CadÚnico para a estimativa dos improvisados, assim como tem sido feito desde o ano de 2016 (FJP, 2021). Porém, a partir do ano de 2023 serão identificados, anualmente, os municípios com valores considerados extremos no que se refere à quantidade de famílias em habitações improvisadas.

A identificação desses municípios extremos só foi possível a partir da divulgação dos dados de população e totais de domicílios por município do Censo de 2022, sendo delineada utilizando a técnica dos *boxplots*. Essa técnica é feita a partir da amplitude interquartil (interquartile range – IQR) das proporções entre famílias em habitações improvisadas (CadÚnico) por total de domicílios ocupados no município (Censo). Mais especificamente, qualquer município, agrupado segundo o porte populacional municipal e a região do Brasil, com proporção menor que três vezes o menor valor do primeiro quartil (Q1), linha inferior da caixa do *boxplot*, ou maior que três vezes o valor do terceiro quartil (Q3), linha superior da caixa do *boxplot*, são considerados extremos. No nosso caso, para ser

---

[3] Primeiro como instrução normativa conjunta Sagicad/Senarc/Snas/MDS n° 4, de 14 de junho de 2023. Mais recentemente com o Decreto n° 12.417.

[4] Em março de 2025 foi lançado, inclusive, o Novo Cadastro Único, que facilita os cruzamentos entre informações de diversas bases de dados do Governo Federal.

considerado “extremo” foram identificados apenas valores três vezes maiores do que o valor do Q3. Para 2023, 580 municípios foram considerados “extremos”. A lista com esses municípios, por Unidade Federativa (UF), está disponível no link: https://docs.google.com/spreadsheets/d/15P6pJiKLLlf1lyoN8Mmnhg6xNaeSZ3mK/edit?usp=sharing&ouid=104372843943715905267&rtpof=true&sd=true.

Após a identificação desses municípios considerados extremos, e a fim de realizar uma correção, utilizou-se princípios da padronização indireta (FJP, 2025). Para estimar as famílias em domicílios improvisados desses municípios, adotou-se a mediana das proporções de improvisados no CadÚnico dos demais municípios do país, por porte populacional e grande região geográfica, como padrão da proporção de improvisados. Ou seja, utilizou-se sete grupos de porte populacional[5] e as cinco grandes regiões do Brasil[6] para gerar 35 medianas como referência para os municípios com valores de proporções extremas. A partir disso, multiplicou-se o total de domicílios particulares ocupados do Censo do município, identificado como extremo pela respectiva mediana, para se obter o total de domicílios improvisados corrigido — para um maior detalhamento consultar FJP (2025).

Finalmente, esta correção das famílias em domicílios improvisados nos municípios extremos, também gerou impacto nas estimativas quanto às características, por renda, cor ou raça e urbano e rural, nos totais estimados. A correção dos dados proposta para os municípios extremos permite a obtenção do total de famílias, mas não o seu detalhamento.

Assim, para realizarmos os cruzamentos das características constantes neste relatório, especificamente para o total de famílias nos municípios padronizados indiretamente, utilizou-se a mesma proporção de cada característica observada para todo o restante das famílias em domicílios improvisados.

[5] As sete categorias de porte populacional municipal, convencionalmente utilizadas pelo IBGE, são: até 5 mil; de 5 mil até 10 mil; de 10 mil até 20 mil; de 20 mil até 50 mil; de 50 mil até 100 mil; de 100 mil até 500 mil; e mais de 500 mil (IBGE, 2018).

[6] Norte, Nordeste, Sudeste, Sul e Centro-Oeste.

3 DÉFICIT HABITACIONAL EM 2023

Em 2023, o déficit habitacional foi estimado em 5.977.317 domicílios, representando 7,6% do total de domicílios particulares ocupados no Brasil. Esse resultado aponta uma redução de 3,8% em relação a 2022, quando foram contabilizados 6.215.313 domicílios em déficit, equivalentes a 8,3%. Conforme exemplificado na Tabela 1, o Sudeste (2,31 milhões) e o Nordeste (1,63 milhões) são as regiões com maiores contingentes absolutos do déficit, seguidas por Norte, Sul e Centro-Oeste. A exemplo do ano anterior, a maior parte do déficit ocorreu fora das regiões metropolitanas (RM).

Na Tabela 1, verificou-se que o componente predominante continua sendo o ônus excessivo com aluguel urbano, que corresponde a 3.665.440 domicílios (61,3%), seguido por habitações precárias (1.241.437) e coabitação (1.070.440). Essa distribuição reforça a tendência já observada nos anos anteriores, em que o ônus vem se consolidando como principal componente do déficit, especialmente nas localidades urbanas e metropolitanas.

Conforme a Tabela 1 e o Mapa 1, as UFs com maiores valores absolutos de déficit habitacional são São Paulo, Rio de Janeiro e Minas Gerais. Já os menores valores absolutos estão em Roraima, Acre e Tocantins.

Tabela 1: Déficit habitacional por componente e total, segundo regiões geográficas, unidades da Federação e regiões metropolitanas – Brasil – 2023

(continua)

Especificação	Habitação precária	Coabitação	Ônus	Déficit habitacional	Déficit habitacional relativo
Norte	**295.393**	**212.614**	**220.900**	**728.906**	**11,9%**
Rondônia	20.119	9.180	27.187	56.486	8,1%
Acre	15.111	6.627	9.155	30.893	10,6%
Amazonas	84.458	58.543	48.082	191.082	14,7%
RM Manaus	*63.828*	*30.540*	*41.722*	*136.089*	*15,3%*
Roraima	5.554	6.804	14.400	26.758	14,9%
Pará	121.829	110.257	94.662	326.749	11,6%
RM Belém	*21.457*	*33.828*	*35.237*	*90.522*	*11,6%*
Amapá	33.478	11.570	5.751	50.799	17,7%
RM Macapá	*23.965*	*8.058*	*4.746*	*36.769*	*17,0%*
Tocantins	14.844	9.633	21.663	46.140	8,1%
Nordeste	**512.201**	**296.159**	**826.282**	**1.634.642**	**7,9%**

Especificação	Habitação precária	Coabitação	Ônus	Déficit habitacional	Déficit habitacional relativo
Maranhão	191.749	53.845	59.893	305.487	13,0%
RM Grande São Luís	*12.571*	*12.411*	*30.523*	*55.505*	*11,0%*
Piauí	52.617	18.084	20.521	91.222	7,9%
Ride Grande Teresina	*7.734*	*9.227*	*8.187*	*25.148*	*6,0%*
Ceará	22.396	45.938	143.139	211.473	6,4%
RM Fortaleza	*3.070*	*22.555*	*78.322*	*103.946*	*7,3%*
Rio Grande do Norte	22.666	22.393	54.565	99.623	7,8%
RM Natal	*2.431*	*11.068*	*31.086*	*44.585*	*8,3%*
Paraíba	27.321	19.485	55.199	102.004	6,8%
RM João Pessoa	*7.345*	*10.114*	*23.254*	*40.713*	*8,5%*
Pernambuco	27.267	41.075	189.753	258.095	7,3%
RM Recife	*3.154*	*16.170*	*92.347*	*111.671*	*7,3%*
Alagoas	36.130	16.968	56.281	109.379	9,2%
RM Maceió	*11.936*	*5.666*	*32.498*	*50.099*	*10,8%*
Sergipe	13.940	7.186	43.496	64.622	7,5%
RM Aracaju	*5.588*	*3.531*	*27.285*	*36.405*	*9,9%*
Bahia	118.116	71.186	203.435	392.737	7,1%
RM Salvador	*13.247*	*15.266*	*77.234*	*105.747*	*6,7%*
Sudeste	**194.283**	**347.052**	**1.772.506**	**2.313.841**	**6,8%**
Minas Gerais	36.249	76.154	366.353	478.756	6,0%
RM Belo Horizonte	*5.266*	*21.884*	*88.486*	*115.637*	*5,7%*
Espírito Santo	5.392	15.277	58.533	79.201	5,2%
RM Grande Vitória	*1794,649392*	*6.855*	*34.066*	*42.716*	*5,6%*
Rio de Janeiro	70.016	86.610	379.339	535.964	7,9%
RM Rio de Janeiro	*62.408*	*67.872*	*271.275*	*401.554*	*8,0%*
São Paulo	82.626	169.012	968.281	1.219.919	7,0%
RM São Paulo	*40.135*	*100.996*	*464.271*	*605.402*	*7,3%*
Sul	**138.224**	**86.205**	**488.383**	**712.812**	**6,2%**
Paraná	55.747	29.032	189.332	274.111	6,4%
RM Curitiba	*12.225*	*10.964*	*60.735*	*83.923*	*6,1%*
Santa Catarina	41.936	27.282	150.573	219.790	8,1%
RM Florianópolis	*3.785*	*6.614*	*30.705*	*41.104*	*9,8%*
Rio Grande do Sul	40.542	29.891	148.479	218.912	4,9%

Especificação	Habitação precária	Coabitação	Ônus	Déficit habitacional	Déficit habitacional relativo
RM Porto Alegre	*7.917*	*8.668*	*49.781*	*66.365*	*3,8%*
Centro-Oeste	**101.336**	**128.410**	**357.369**	**587.115**	**9,5%**
Mato Grosso do Sul	12.969	15.903	53.718	82.590	8,0%
Mato Grosso	61.611	29.467	74.198	165.276	12,9%
RM Vale do Rio Cuiabá	*3.578*	*15.250*	*16.526*	*35.354*	*10,6%*
Goiás	20.740	66.996	144.565	232.301	8,5%
RM Goiânia	*3.273*	*34.430*	*64.118*	*101.821*	*10,0%*
Distrito Federal	6.016	16.043	84.889	106.948	9,4%
Brasil	**1.241.437**	**1.070.440**	**3.665.440**	**5.977.317**	**7,6%**
Total das RM	*316.707*	*451.966*	*1.562.404*	*2.331.076*	*7,7%*
Demais áreas	*924.730*	*618.474*	*2.103.036*	*3.646.240*	*7,6%*

Fonte: Dados básicos: Instituto Brasileiro de Geografia e Estatística (2024); CadÚnico (2023). Elaboração própria.

O déficit relativo também apresenta variações significativas. A partir da Tabela 1, em 2023, o maior índice é observado na região Norte (11,9%), seguida do Centro-Oeste (9,5%), Nordeste (7,9%), Sudeste (6,8%), e Sul (6,2%). As UFs com menores valores de déficit relativos são: Rio Grande do Sul, Espírito Santo e Minas Gerais. Enquanto aquelas com maiores valores relativos são: Amapá, Roraima e Amazonas. Destaca-se que embora Roraima tenha um dos menores valores absolutos, em termos relativos está entre os três maiores, indicando a importância da leitura conjunta dos dados.

Mapa 1: Déficit habitacional total por unidades da Federação – Brasil – 2023

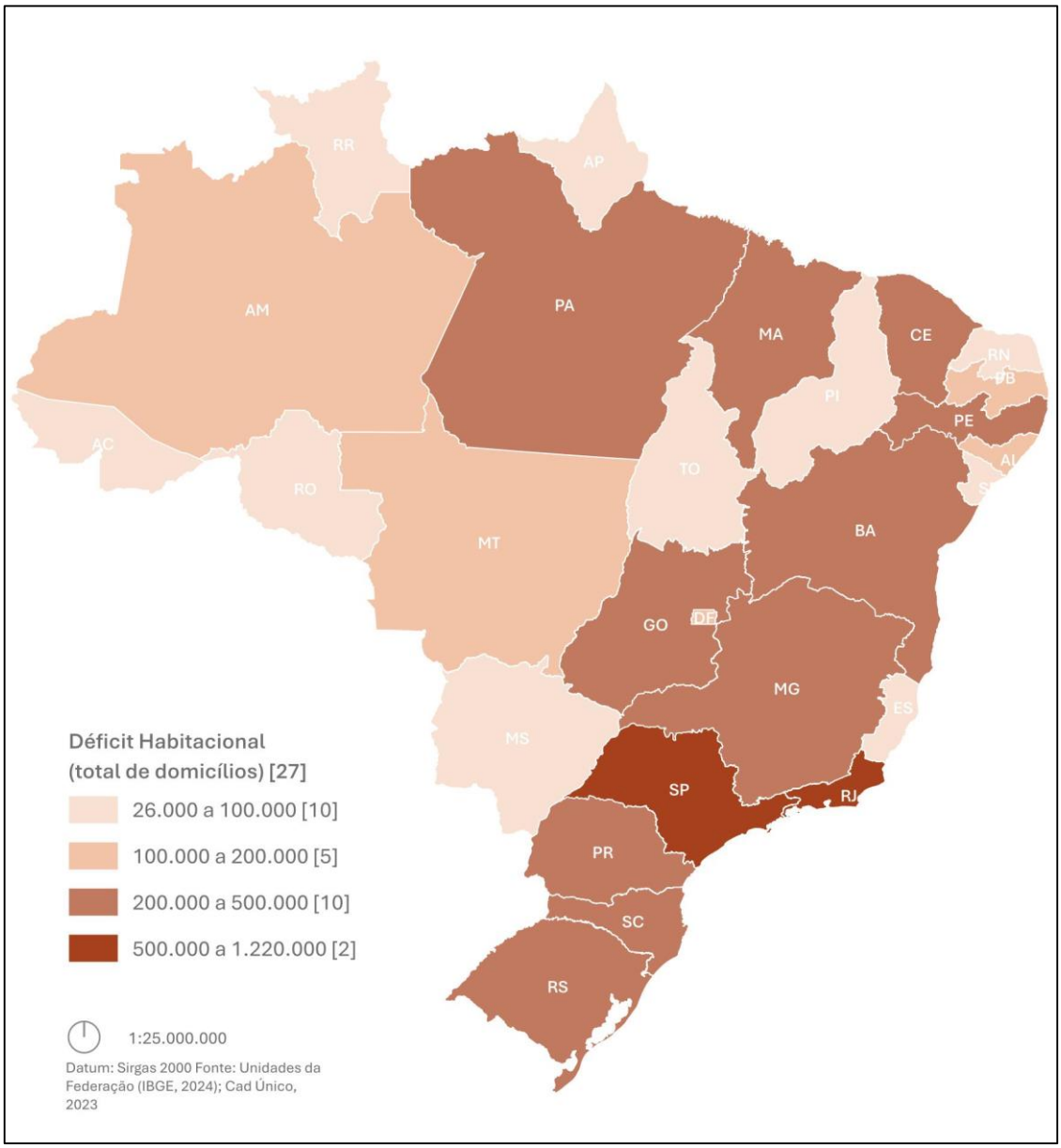

Fonte: Dados básicos: Instituto Brasileiro de Geografia e Estatística (2024); CadÚnico (2023). Elaboração própria.

Com relação ao principal componente que contribui em termos absolutos para o déficit habitacional, observa-se, no Mapa 2, que das 27 UFs, 22 apresentam o ônus excessivo como principal componente, 4 UFs têm habitação precária como predominantes, e 1 UF (Pará) tem coabitação como maior componente. Assim como em 2022, apenas nas regiões Norte e Nordeste é possível observar UFs com predomínio dos componentes de habitação precária ou coabitação. Isso reforça, mais uma

vez, a diversidade regional do déficit habitacional brasileiro e a permanência de padrões estruturais diferenciados de manifestação do déficit habitacional entre as regiões do país.

Mapa 2: Principal componente do déficit habitacional por unidade da Federação – 2023

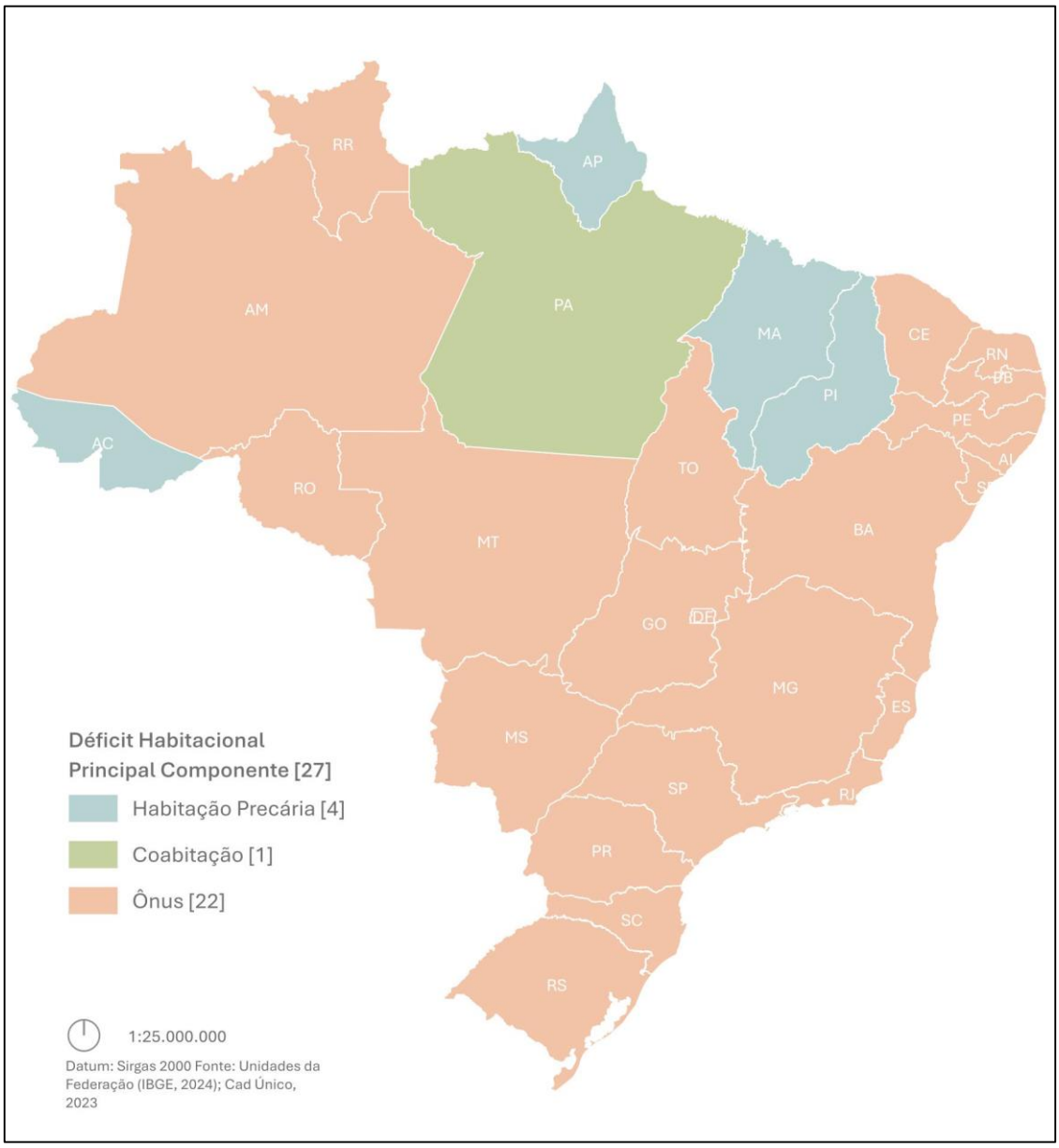

Fonte: Dados básicos: Instituto Brasileiro de Geografia e Estatística (2024); CadÚnico (2023). Elaboração própria.

Por fim, o Mapa 3 apresenta o déficit habitacional relativo, a razão entre o total de domicílios em situação de déficit habitacional e o total de domicílios particulares ocupados. A partir dele, depreende-se que o indicador do déficit habitacional relativo é maior na região Norte, seguido

pelo Nordeste (Maranhão e Alagoas) e Centro-Oeste (Distrito Federal e Goiás), e posteriormente por outros estados nordestinos, além de outras UFs do Centro-Oeste, Sudeste e Sul.

Mapa 3: Déficit habitacional relativo ao total de domicílios particulares ocupados (permanentes e improvisados) – unidades da Federação – 2023



Fonte: Dados básicos: Instituto Brasileiro de Geografia e Estatística (2024); CadÚnico (2023). Elaboração própria.

Com a finalidade de aprofundar a análise espacial do déficit habitacional em 2023, os dados foram desagregados segundo os estratos geográficos definidos pelo Instituto Brasileiro de

Geografia e Estatística (IBGE) na PnadC. Esses estratos correspondem a 146 divisões territoriais dentro das UFs, construídas com o intuito de reunir municípios com características semelhantes entre si e garantir que cada área possua coerência geográfica e utilidade para fins analíticos. Em termos práticos, esses recortes representam uma escala intermediária entre o nível estadual e o municipal, com respaldo estatístico adequado para análises regionais.

O Mapa 4 apresenta o déficit habitacional relativo por estrato geográfico dividido por quartil. A partir dele, é possível notar como os maiores déficits habitacionais relativos se encontram em estratos geográficos localizados no Norte do país. Além disso, há áreas pontuais com altos índices no estado do Mato Grosso e em alguns estados do Centro-Oeste, além de trechos do litoral do Nordeste, especialmente entre Alagoas e Bahia, e em partes do Espirito Santo. Todavia, no Sudeste os estados de Minas Gerais, São Paulo e Rio de Janeiro apresentam, predominantemente, baixos percentuais de déficit relativo, com poucas exceções localizadas, assim como nos estados do Sul do país. Essa configuração se assemelha à observada em 2022, especialmente no que diz respeito à concentração de altos percentuais na região Norte e no estado do Mato Grosso.

Ao comparar o Mapa 3 com o Mapa 4, é possível perceber que os dois mapas reforçam que o Norte do país concentra os maiores percentuais de déficit habitacional relativo. Os estados de Mato Grosso e Maranhão também estão entre os mais afetados, com destaque em ambos os mapas.

Mapa 4: Déficit habitacional relativo ao total de domicílios particulares ocupados (permanentes e improvisados) por estrato geográfico do IBGE – 2023

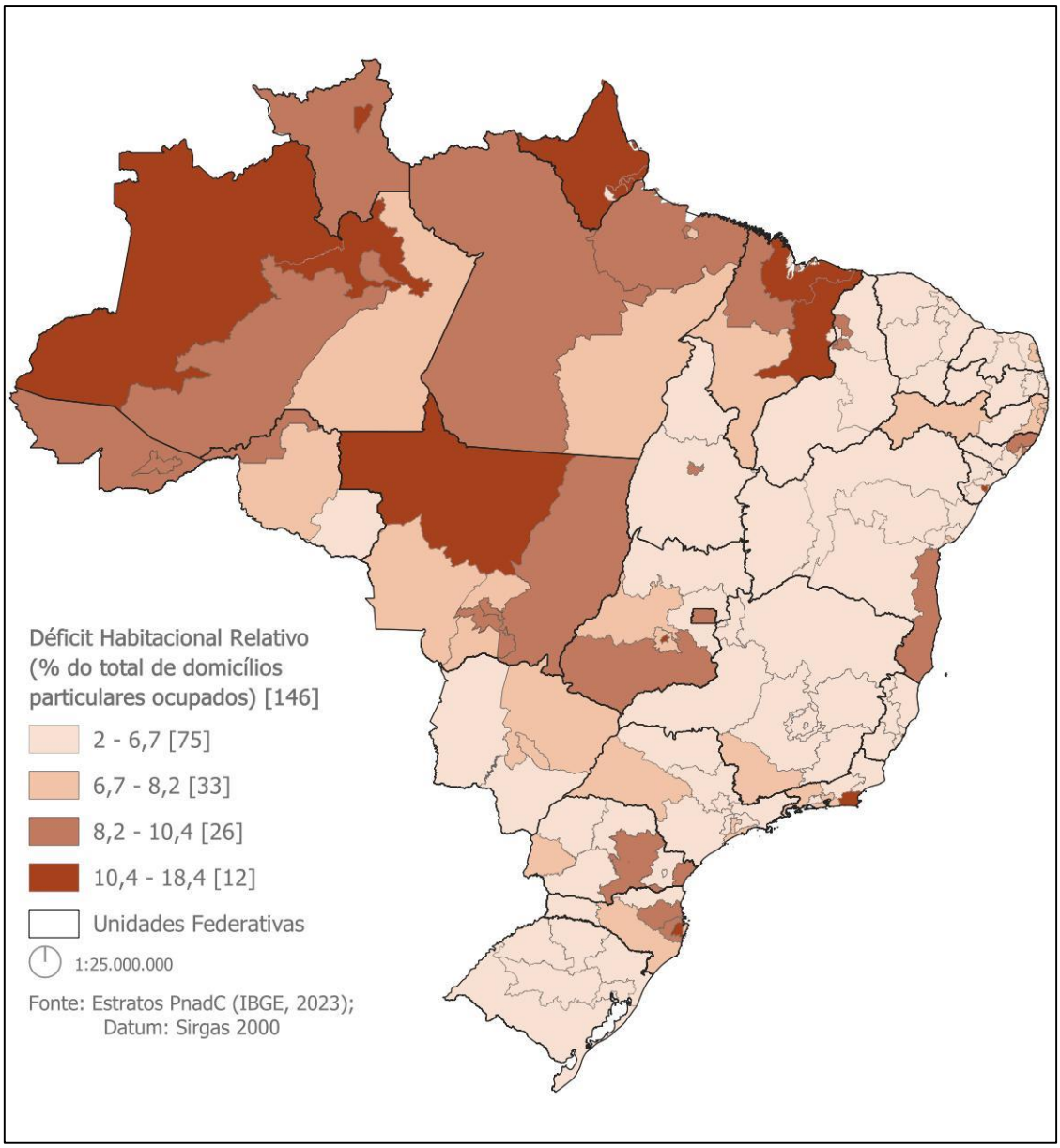

Fonte: Dados básicos: Instituto Brasileiro de Geografia e Estatística (2024); CadÚnico (2023). Elaboração própria.

O Mapa 5 apresenta os principais componentes do déficit habitacional por estrato geográfico, confirmando a predominância do ônus excessivo com aluguel urbano como principal fator em grande parte do território nacional. Esse componente é o principal em 123 estratos, seguido pela habitação precária, presente em 13 estratos, e pela coabitação, que aparece como principal componente em 10 estratos.

Ademais, além da destacada diferenciação regional com o ônus excessivo com aluguel urbano predominando nas regiões Sudeste, Sul e Centro-Oeste, verifica-se também as diversidades intraestaduais de manifestação do déficit habitacional. Por exemplo, nos estratos geográficos mais densos do Norte, isto é, as capitais e RMs, o principal componente é o ônus excessivo com aluguel, contrastando com os demais estratos de suas UFs em que o principal componente é a habitação precária ou a coabitação.

Mapa 5: Principal componente do déficit habitacional por estrato geográfico do IBGE – 2023

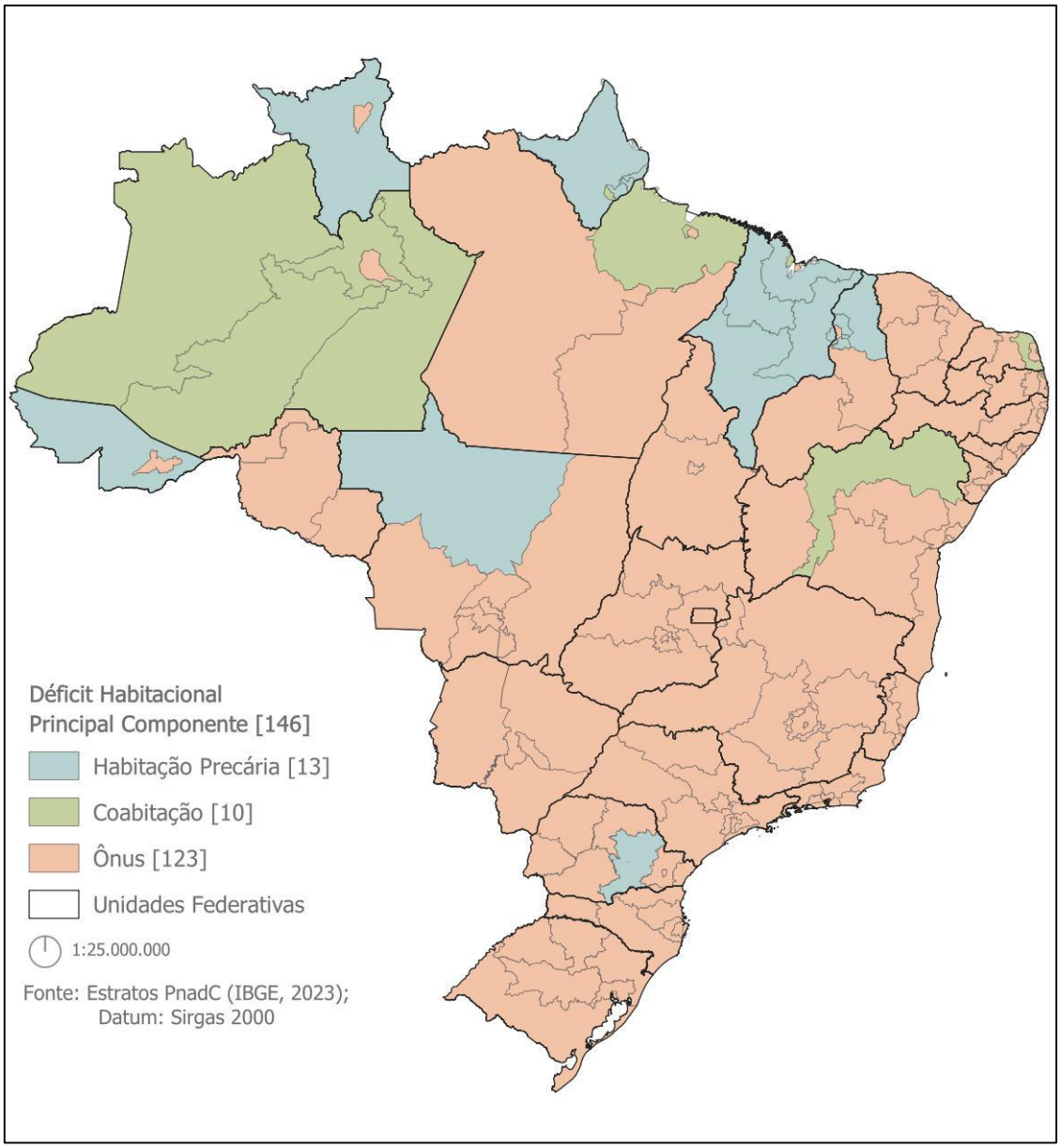

Fonte: Dados básicos: Instituto Brasileiro de Geografia e Estatística (2024); CadÚnico (2023). Elaboração própria.

A Tabela 2 evidencia a diversidade regional do déficit habitacional no Brasil em 2023, padrão já observado em 2022. O ônus excessivo com aluguel urbano segue como principal componente nacional (61,3%), com destaque para as regiões Sudeste (76,6%), Sul (68,5%) e Centro-Oeste (60,9%), especialmente nas áreas urbanas, já que esse padrão se manteve estável em relação a 2022.

Na região Norte (40,5%), predomina a habitação precária. Isso reflete a precariedade do parque habitacional regional. Já no Nordeste, embora o componente predominante seja o ônus excessivo com aluguel (50,5%), a habitação precária apresenta uma participação significativa (31,3%), o que demonstra a precariedade de acesso à moradia nessas regiões. Os estados do Maranhão (62,8%), Amapá (65,9%) e Piauí (57,7%) mantêm os maiores percentuais de habitação precária, semelhante ao observado no ano anterior. Já a coabitação, embora minoritária no total domiciliar (17,9%), destaca-se em alguns estados, como Pará (33,7%) e a Região Integrada de Desenvolvimento (Ride) da Grande Teresina (36,7%).

Assim como no ano de 2022, as RM apresentam maior concentração do ônus excessivo com aluguel, enquanto as áreas não metropolitanas concentram habitação precária, evidenciando desigualdades intraestaduais.

Tabela 2: Composição do déficit habitacional por componente, segundo regiões geográficas, unidades da Federação e regiões metropolitanas – Brasil – 2023

(continua)

Especificação	Habitação precária	Coabitação	Ônus
Norte	**40,5%**	**29,2%**	**30,3%**
Rondônia	35,6%	16,3%	48,1%
Acre	48,9%	21,5%	29,6%
Amazonas	44,2%	30,6%	25,2%
RM Manaus	*46,9%*	*22,4%*	*30,7%*
Roraima	20,8%	25,4%	53,8%
Pará	37,3%	33,7%	29,0%
RM Belém	*23,7%*	*37,4%*	*38,9%*
Amapá	65,9%	22,8%	11,3%
RM Macapá	*65,2%*	*21,9%*	*12,9%*
Tocantins	32,2%	20,9%	47,0%
Nordeste	**31,3%**	**18,1%**	**50,5%**
Maranhão	62,8%	17,6%	19,6%

Especificação	Habitação precária	Coabitação	Ônus
RM Grande São Luís	*22,6%*	*22,4%*	*55,0%*
Piauí	57,7%	19,8%	22,5%
Ride Grande Teresina	*30,8%*	*36,7%*	*32,6%*
Ceará	10,6%	21,7%	67,7%
RM Fortaleza	*3,0%*	*21,7%*	*75,3%*
Rio Grande do Norte	22,8%	22,5%	54,8%
RM Natal	*5,5%*	*24,8%*	*69,7%*
Paraíba	26,8%	19,1%	54,1%
RM João Pessoa	*18,0%*	*24,8%*	*57,1%*
Pernambuco	10,6%	15,9%	73,5%
RM Recife	*2,8%*	*14,5%*	*82,7%*
Alagoas	33,0%	15,5%	51,5%
RM Maceió	*23,8%*	*11,3%*	*64,9%*
Sergipe	21,6%	11,1%	67,3%
RM Aracaju	*15,4%*	*9,7%*	*74,9%*
Bahia	30,1%	18,1%	51,8%
RM Salvador	*12,5%*	*14,4%*	*73,0%*
Sudeste	**8,4%**	**15,0%**	**76,6%**
Minas Gerais	7,6%	15,9%	76,5%
RM Belo Horizonte	*4,6%*	*18,9%*	*76,5%*
Espírito Santo	6,8%	19,3%	73,9%
RM Grande Vitória	*4,2%*	*16,0%*	*79,8%*
Rio de Janeiro	13,1%	16,2%	70,8%
RM Rio de Janeiro	*15,5%*	*16,9%*	*67,6%*
São Paulo	6,8%	13,9%	79,4%
RM São Paulo	*6,6%*	*16,7%*	*76,7%*
Sul	**19,4%**	**12,1%**	**68,5%**
Paraná	20,3%	10,6%	69,1%
RM Curitiba	*14,6%*	*13,1%*	*72,4%*
Santa Catarina	19,1%	12,4%	68,5%
RM Florianópolis	*9,2%*	*16,1%*	*74,7%*
Rio Grande do Sul	18,5%	13,7%	67,8%
RM Porto Alegre	*11,9%*	*13,1%*	*75,0%*
Centro-Oeste	**17,3%**	**21,9%**	**60,9%**

Especificação	Habitação precária	Coabitação	Ônus
Mato Grosso do Sul	15,7%	19,3%	65,0%
Mato Grosso	37,3%	17,8%	44,9%
RM Vale do Rio Cuiabá	*10,1%*	*43,1%*	*46,7%*
Goiás	8,9%	28,8%	62,2%
RM Goiânia	*3,2%*	*33,8%*	*63,0%*
Distrito Federal	5,6%	15,0%	79,4%
Brasil	**20,8%**	**17,9%**	**61,3%**
Total das RM	*13,6%*	*19,4%*	*67,0%*
Demais áreas	*25,4%*	*17,0%*	*57,7%*

Fonte: Dados básicos: Instituto Brasileiro de Geografia e Estatística (2024); CadÚnico (2023). Elaboração própria.

3.1 Déficit habitacional por situação (urbano e rural)

A localização dos domicílios em situação de déficit habitacional revela importantes contrastes regionais no Brasil. Assim, conforme o Gráfico 1 e a Tabela 3, observa-se que o déficit habitacional brasileiro permanece majoritariamente urbano (89,5%), especialmente nas regiões Sudeste, Sul e Centro Oeste, onde a maioria dos estados apresentam mais de 90% do déficit habitacional em áreas urbanas.

Todavia, em contraste as regiões Norte (19,9%) e Nordeste (21,7%) a participação rural é mais significativa, destacando os estados como Maranhão, Piauí, Pará e Bahia, que também possuem altos índices de habitação precária. Esses dados reforçam a relação entre déficit habitacional rural e habitação precária, enquanto nas áreas urbanas e metropolitanas o déficit habitacional é mais ligado aos gastos com o aluguel em relação à renda domiciliar.

Gráfico 1: Distribuição do déficit habitacional por situação de domicílio, segundo regiões geográficas – Brasil – 2023

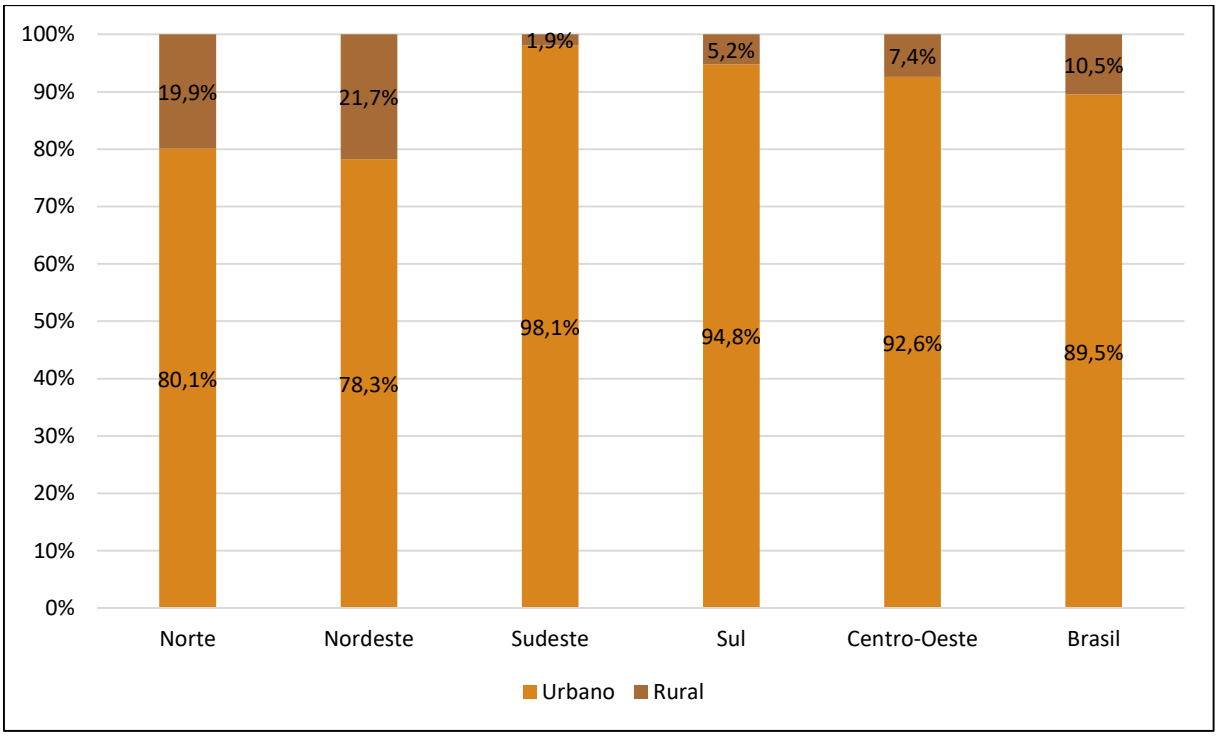

Fonte: Dados básicos: Instituto Brasileiro de Geografia e Estatística (2024); CadÚnico (2023). Elaboração própria.

Tabela 3: Déficit habitacional por situação de domicílio, segundo regiões geográficas, unidades da Federação e regiões metropolitanas – Brasil – 2023

(continua)

Especificação	Total			Composição	
	Urbano	Rural	**Total**	Urbano	Rural
Norte	**583.985**	**144.921**	**728.906**	**80,1%**	**19,9%**
Rondônia	47.054	9.432	56.486	83,3%	16,7%
Acre	24.788	6.105	30.893	80,2%	19,8%
Amazonas	164.949	26.133	191.082	86,3%	13,7%
RM Manaus	*125.123*	*10.967*	*136.089*	*91,9%*	*8,1%*
Roraima	23.518	3.241	26.758	87,9%	12,1%
Pará	238.146	88.602	326.749	72,9%	27,1%
RM Belém	*89.594*	*928*	*90.522*	*99,0%*	*1,0%*
Amapá	45.981	4.818	50.799	90,5%	9,5%
RM Macapá	*35.575*	*1.194*	*36.769*	*96,8%*	*3,2%*

Especificação	Total			Composição	
	Urbano	Rural	**Total**	Urbano	Rural
Tocantins	39.550	6.590	46.140	85,7%	14,3%
Nordeste	**1.279.623**	**355.019**	**1.634.642**	**78,3%**	**21,7%**
Maranhão	163.751	141.736	305.487	53,6%	46,4%
RM Grande São Luís	*52.896*	*2.609*	*55.505*	*95,3%*	*4,7%*
Piauí	50.823	40.399	91.222	55,7%	44,3%
RIDE Grande Teresina	*19.288*	*5.861*	*25.148*	*76,7%*	*23,3%*
Ceará	183.970	27.503	211.473	87,0%	13,0%
RM Fortaleza	*103.216*	*730*	*103.946*	*99,3%*	*0,7%*
Rio Grande do Norte	86.194	13.429	99.623	86,5%	13,5%
RM Natal	*43.442*	*1.143*	*44.585*	*97,4%*	*2,6%*
Paraíba	89.629	12.375	102.004	87,9%	12,1%
RM João Pessoa	*39.619*	*1.095*	*40.713*	*97,3%*	*2,7%*
Pernambuco	236.671	21.423	258.095	91,7%	8,3%
RM Recife	*111.393*	*278*	*111.671*	*99,8%*	*0,2%*
Alagoas	91.283	18.096	109.379	83,5%	16,5%
RM Maceió	*49.354*	*745*	*50.099*	*98,5%*	*1,5%*
Sergipe	56.137	8.485	64.622	86,9%	13,1%
RM Aracaju	*34.714*	*1.691*	*36.405*	*95,4%*	*4,6%*
Bahia	321.164	71.573	392.737	81,8%	18,2%
RM Salvador	*104.208*	*1.539*	*105.747*	*98,5%*	*1,5%*
Sudeste	**2.269.218**	**44.623**	**2.313.841**	**98,1%**	**1,9%**
Minas Gerais	461.637	17.119	478.756	96,4%	3,6%
RM Belo Horizonte	*115.101*	*535*	*115.637*	*99,5%*	*0,5%*
Espírito Santo	75.461	3.740	79.201	95,3%	4,7%
RM Grande Vitória	*42.669*	*47*	*42.716*	*99,9%*	*0,1%*
Rio de Janeiro	532.644	3.320	535.964	99,4%	0,6%
RM Rio de Janeiro	*400.867*	*687*	*401.554*	*99,8%*	*0,2%*
São Paulo	1.199.475	20.444	1.219.919	98,3%	1,7%
RM São Paulo	*603.474*	*1.927*	*605.402*	*99,7%*	*0,3%*
Sul	**675.659**	**37.153**	**712.812**	**94,8%**	**5,2%**
Paraná	261.118	12.992	274.111	95,3%	4,7%
RM Curitiba	*83.160*	*764*	*83.923*	*99,1%*	*0,9%*
Santa Catarina	208.106	11.683	219.790	94,7%	5,3%

Especificação	Total			Composição	
	Urbano	Rural	**Total**	Urbano	Rural
RM Florianópolis	*40.948*	*156*	*41.104*	*99,6%*	*0,4%*
Rio Grande do Sul	206.435	12.478	218.912	94,3%	5,7%
RM Porto Alegre	*66.064*	*301*	*66.365*	*99,5%*	*0,5%*
Centro-Oeste	**543.560**	**43.555**	**587.115**	**92,6%**	**7,4%**
Mato Grosso do Sul	76.806	5.784	82.590	93,0%	7,0%
Mato Grosso	141.009	24.267	165.276	85,3%	14,7%
RM Vale do Rio Cuiabá	*33.637*	*1.716*	*35.354*	*95,1%*	*4,9%*
Goiás	223.655	8.646	232.301	96,3%	3,7%
RM Goiânia	*101.635*	*187*	*101.821*	*99,8%*	*0,2%*
Distrito Federal	102.090	4.859	106.948	95,5%	4,5%
Brasil	**5.352.044**	**625.272**	**5.977.317**	**89,5%**	**10,5%**
Total das RM	*2.295.975*	*35.101*	*2.331.076*	*98,5%*	*1,5%*
Demais áreas	*3.056.069*	*590.171*	*3.646.240*	*83,8%*	*16,2%*

Fonte: Dados básicos: Instituto Brasileiro de Geografia e Estatística (2024); CadÚnico (2023). Elaboração própria.

3.2 Déficit habitacional por faixa de renda de salário mínimo domiciliar

Os recortes por faixas de renda domiciliar utilizados neste relatório consideraram a divisão por salários mínimos (SM)[7] da seguinte forma:

a) até um SM de renda domiciliar,

b) entre um e dois SM de renda domiciliar,

c) entre dois e três SM de renda domiciliar;

d) acima de três SM de renda domiciliar.

O Gráfico 2 demonstra como o déficit habitacional brasileiro está concentrado nos domicílios na faixa de renda entre um e dois SM, especialmente nas regiões Sudeste, Sul e Centro-Oeste. A participação nacional neste recorte salarial é de 38,8%, alcançando 45,9% na região Sudeste.

[7] Foi levado em consideração o valor do salário mínimo referente a janeiro do referido 2023, de R$1.302,00, conforme metodologia estabelecida pelo Relatório Metodológico do Déficit Habitacional e Inadequação de Domicílios no Brasil para os anos de 2016 a 2019 (FJP, 2021).

Por outro lado, as regiões Norte e Nordeste apresentam participação maior no segmento de renda de até um SM. Ao compararmos com o ano de 2022[8], quando a Faixa 1 abrangia domicílios com renda bruta familiar mensal de até R$ 2.640,00, percebe-se que o padrão de concentração do déficit permanece. A divisão atual, que separa os domicílios com renda entre um e dois SM daqueles com renda inferior a um SM, permite uma análise mais detalhada do comportamento desse grupo de menor renda.

Gráfico 2: Composição relativa, por faixa de renda de salário mínimo domiciliar, do déficit habitacional, segundo regiões geográficas – Brasil – 2023

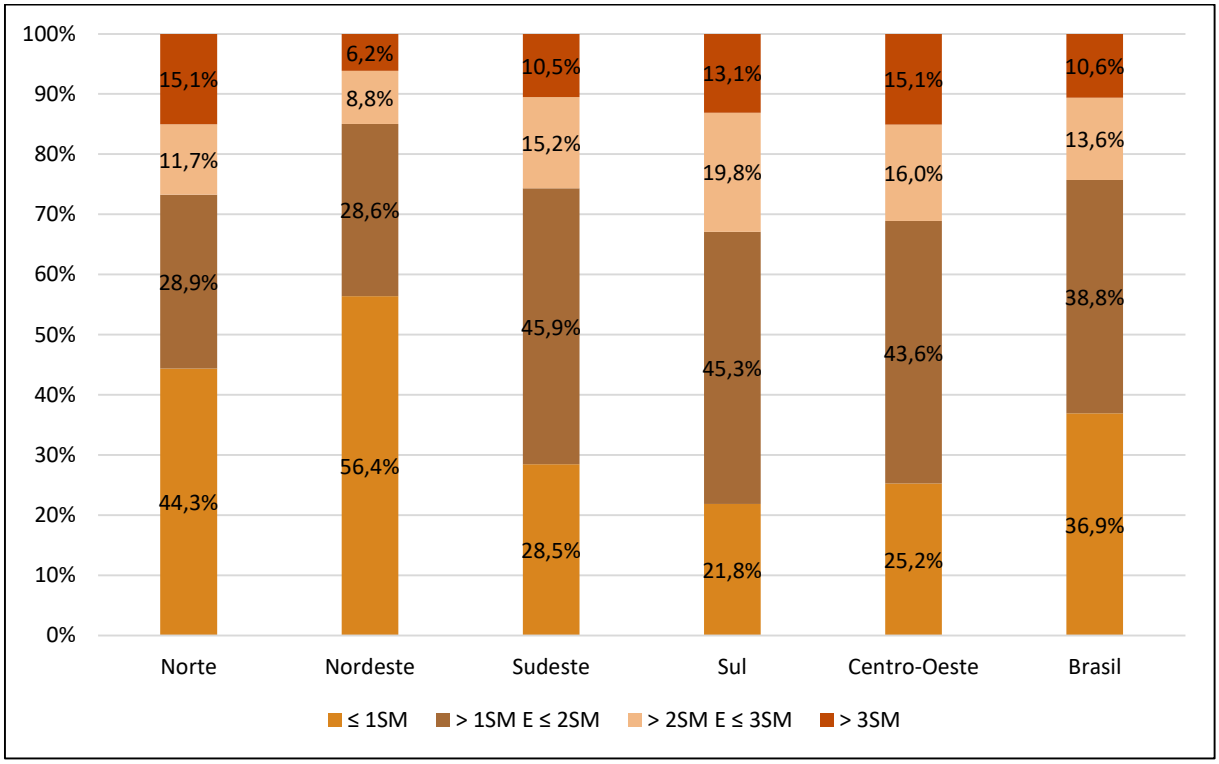

Fonte: Dados básicos: Instituto Brasileiro de Geografia e Estatística (2024); CadÚnico (2023). Elaboração própria.

As Tabelas 4 e 5 cruzam os componentes do déficit habitacional com as faixas de renda domiciliar em SM, evidenciando o predomínio dos domicílios com renda de até um SM na habitação precária. No caso do componente de ônus excessivo com aluguel urbano, vemos uma predominância na faixa de renda de um até dois SM. Já no caso da coabitação, observa-se maior presença dos

[8] Os recortes por faixas de renda domiciliar utilizados no relatório de 2022 foram definidos com base no art. 5°, inciso I, da Lei n° 14.620, de 13 de julho de 2023, que regulamenta o Programa Minha Casa, Minha Vida (MCMV) para áreas urbanas.

domicílios com renda superior a três SM, especialmente entre aqueles com rendimentos entre dois e três SM e acima de três SM. O padrão da predominância nessas faixas de salário continua tanto nacionalmente, quanto nas RM.

Tabela 4: Déficit habitacional, por faixa de renda de salário mínimo domiciliar, segundo regiões geográficas – Brasil – 2023

(continua)

Especificação	Componente	Faixa de renda				
		≤ 1SM	> 1SM e ≤ 2SM	> 2SM e ≤ 3SM	> 3SM	Total
Norte	Precários	189.338	73.416	21.937	10.702	295.393
	Coabitação	23.629	45.060	44.883	99.042	212.614
	Ônus	110.297	92.392	18.211	-	220.900
	Déficit	**323.264**	**210.868**	**85.031**	**109.743**	**728.906**
Nordeste	Precários	319.799	141.531	37.706	13.165	512.201
	Coabitação	51.239	87.490	69.796	87.634	296.159
	Ônus	551.154	238.570	36.558	-	826.282
	Déficit	**922.191**	**467.591**	**144.060**	**100.799**	**1.634.641**
Sudeste	Precários	105.842	58.928	17.595	11.917	194.282
	Coabitação	16.561	62.641	36.268	231.582	347.052
	Ônus	536.190	939.564	296.752	-	1.772.506
	Déficit	**658.593**	**1.061.133**	**350.615**	**243.499**	**2.313.840**
Sul	Precários	38.181	37.916	29.465	32.663	138.225
	Coabitação	2.390	11.129	11.947	60.739	86.205
	Ônus	115.168	273.557	99.658	-	488.383
	Déficit	**155.739**	**322.603**	**141.070**	**93.402**	**712.814**
Centro-Oeste	Precários	35.284	19.791	10.237	36.024	101.336
	Coabitação	12.151	31.418	32.412	52.429	128.410
	Ônus	100.788	205.050	51.531	-	357.369
	Déficit	**148.224**	**256.259**	**94.180**	**88.452**	**587.115**
Brasil	Precários	688.444	331.583	116.940	104.470	1.241.437
	Coabitação	105.971	237.738	195.306	531.425	1.070.440
	Ônus	1.413.597	1.749.133	502.710	-	3.665.440
	Déficit	**2.208.011**	**2.318.454**	**814.956**	**635.895**	**5.977.316**
Total das RM	Precários	204.415	73.526	18.746	20.021	316.708

Especificação	Componente	Faixa de renda				
		≤ 1SM	> 1SM e ≤ 2SM	> 2SM e ≤ 3SM	> 3SM	Total
	Coabitação	41.778	86.423	82.052	241.713	451.966
	Ônus	574.577	753.246	234.580	-	1.562.403
	Déficit	**820.770**	**913.195**	**335.378**	**261.733**	**2.331.076**
Demais áreas	Precários	484.029	258.057	98.195	84.449	924.730
	Coabitação	64.192	151.316	113.254	289.712	618.474
	Ônus	839.020	995.887	268.130	-	2.103.037
	Déficit	**1.387.241**	**1.405.259**	**479.579**	**374.162**	**3.646.241**

Fonte: Dados básicos: Instituto Brasileiro de Geografia e Estatística (2024); CadÚnico (2023). Elaboração própria.

Tabela 5: Déficit habitacional, composição por faixa de renda de salário mínimo domiciliar, segundo regiões geográficas – Brasil – 2023

(continua)

Especificação	Componente	Faixa de renda				
		≤ 1SM	> 1SM e ≤ 2SM	> 2SM e ≤ 3SM	> 3SM	Total
Norte	Precários	64,1%	24,9%	7,4%	3,6%	100,0%
	Coabitação	11,1%	21,2%	21,1%	46,6%	100,0%
	Ônus	49,9%	41,8%	8,2%	-	100,0%
	Déficit	**44,3%**	**28,9%**	**11,7%**	**15,1%**	**100,0%**
Nordeste	Precários	62,4%	27,6%	7,4%	2,6%	100,0%
	Coabitação	17,3%	29,5%	23,6%	29,6%	100,0%
	Ônus	66,7%	28,9%	4,4%	-	100,0%
	Déficit	**56,4%**	**28,6%**	**8,8%**	**6,2%**	**100,0%**
Sudeste	Precários	54,5%	30,3%	9,1%	6,1%	100,0%
	Coabitação	4,8%	18,0%	10,5%	66,7%	100,0%
	Ônus	30,3%	53,0%	16,7%	-	100,0%
	Déficit	**28,5%**	**45,9%**	**15,2%**	**10,5%**	**100,0%**
Sul	Precários	27,6%	27,4%	21,3%	23,6%	100,0%
	Coabitação	2,8%	12,9%	13,9%	70,5%	100,0%
	Ônus	23,6%	56,0%	20,4%	-	100,0%
	Déficit	**21,8%**	**45,3%**	**19,8%**	**13,1%**	**100,0%**

Especificação	Componente	Faixa de renda				
		≤ 1SM	> 1SM e ≤ 2SM	> 2SM e ≤ 3SM	> 3SM	Total
Centro-Oeste	Precários	34,8%	19,5%	10,1%	35,5%	100,0%
	Coabitação	9,5%	24,5%	25,2%	40,8%	100,0%
	Ônus	28,2%	57,4%	14,4%	-	100,0%
	Déficit	**25,2%**	**43,6%**	**16,0%**	**15,1%**	**100,0%**
Brasil	Precários	55,5%	26,7%	9,4%	8,4%	100,0%
	Coabitação	9,9%	22,2%	18,2%	49,6%	100,0%
	Ônus	38,6%	47,7%	13,7%	-	100,0%
	Déficit	**36,9%**	**38,8%**	**13,6%**	**10,6%**	**100,0%**
Total das RM	Precários	64,5%	23,2%	5,9%	6,3%	100,0%
	Coabitação	9,2%	19,1%	18,2%	53,5%	100,0%
	Ônus	36,8%	48,2%	15,0%	-	100,0%
	Déficit	**35,2%**	**39,2%**	**14,4%**	**11,2%**	**100,0%**
Demais áreas	Precários	52,3%	27,9%	10,6%	9,1%	100,0%
	Coabitação	10,4%	24,5%	18,3%	46,8%	100,0%
	Ônus	39,9%	47,4%	12,7%	-	100,0%
	Déficit	**38,0%**	**38,5%**	**13,2%**	**10,3%**	**100,0%**

Fonte: Dados básicos: Instituto Brasileiro de Geografia e Estatística (2024); CadÚnico (2023). Elaboração própria.

A Tabela 6 apresenta as taxas específicas do déficit habitacional, indicando quantos domicílios, a cada mil, encontram-se em situação de déficit habitacional dentro de cada faixa de renda domiciliar. Os domicílios com renda de até um SM se destacam como os mais impactados, concentrando as maiores taxas em todas as regiões do país — áreas metropolitanas e nas demais áreas urbanas. Isso significa que, embora existam mais domicílios em números absolutos em situação de déficit na faixa de um a dois SM, os domicílios com renda inferior a um SM enfrentam uma probabilidade maior de vivenciar essa condição. Ainda assim, a faixa de renda entre um e dois SM também registra elevada incidência, com destaque para as regiões Sudeste, Sul e Centro-Oeste, onde mais de cem domicílios a cada mil estão em situação de déficit habitacional.

Tabela 6: Taxas específicas[9] do déficit habitacional[(1)] por faixa de renda de salário mínimo domiciliar, por 1.000 domicílios particulares ocupados, segundo regiões geográficas – Brasil – 2023

Especificação	Taxa específica por 1.000 domicílios particulares ocupados (DPO)			
	≤ 1SM	> 1SM e ≤ 2SM	> 2SM e ≤ 3SM	> 3SM
Norte	234,61	98,63	36,48	1,68
Nordeste	150,38	58,20	20,42	14,14
Sudeste	195,92	142,89	53,77	6,42
Sul	174,80	147,32	59,56	1,92
Centro-Oeste	257,59	186,45	69,36	24,69
Brasil	**179,16**	**112,80**	**45,77**	**4,01**
Total das RMs	*203,36*	*131,65*	*54,14*	*2,40*
Demais áreas	*167,30*	*102,94*	*41,22*	*5,29*

Fonte: Dados básicos: Instituto Brasileiro de Geografia e Estatística (2024); CadÚnico (2023). Elaboração própria.
(1) Exceto unidades domésticas conviventes déficit.

3.3 **Déficit habitacional por sexo do responsável pelo domicílio**

Conforme a Tabela 7, a distribuição do déficit habitacional por sexo do responsável pelo domicílio mostra o predomínio, em todos os componentes e em todas as regiões dos domicílios, da mulher como responsável pelo domicílio, exceto habitação precária na região Sul e coabitação na Centro-Oeste. Assim, o indicador geral tem 3,69 milhões de domicílios onde uma mulher é responsável (61,8%) e 2,27 milhões onde o responsável é um homem (38,1%).

Particularmente notável é que, para todas as regiões, o componente com maior participação relativa, no qual a pessoa de referência do domicílio é mulher, é o ônus excessivo com o aluguel urbano. A predominância da responsabilidade feminina também se destaca em domicílios em situação de coabitação no Norte, Nordeste e Sudeste, chegando a praticamente 60% no Norte e mais de 60% no Nordeste e no Sudeste. Já com relação à responsabilidade domiciliar feminina das habitações precárias, é a região Centro-Oeste que se destaca com 58,3%.

[9] As taxas específicas são calculadas a partir do total de domicílios em situação de déficit por faixa de renda específica dividido pelo total de domicílios particulares ocupados naquela faixa de renda multiplicados por mil.

Tabela 7: Déficit habitacional por sexo do responsável pelo domicílio, segundo regiões geográficas – Brasil – 2023

(continua)

Especificação	Componente	Total			Composição		
		Homem	Mulher	Ignorado	Homem	Mulher	Ignorado
Norte	Precários	126.900	165.911	2.581	43,0%	56,2%	0,9%
	Coabitação	86.021	126.593	0	40,5%	59,5%	0,0%
	Ônus	88.548	132.352	0	40,1%	59,9%	0,0%
	Déficit	**301.469**	**424.856**	**2.581**	**41,4%**	**58,3%**	**0,4%**
Nordeste	Precários	233.931	275.424	2.846	45,7%	53,8%	0,6%
	Coabitação	105.702	190.457	0	35,7%	64,3%	0,0%
	Ônus	268.506	557.776	0	32,5%	67,5%	0,0%
	Déficit	**608.139**	**1.023.657**	**2.846**	**37,2%**	**62,6%**	**0,2%**
Sudeste	Precários	90.979	101.890	1.414	46,8%	52,4%	0,7%
	Coabitação	132.236	214.816	0	38,1%	61,9%	0,0%
	Ônus	623.693	1.148.813	0	35,2%	64,8%	0,0%
	Déficit	**846.908**	**1.465.519**	**1.414**	**36,6%**	**63,3%**	**0,1%**
Sul	Precários	73.368	64.317	539	53,1%	46,5%	0,4%
	Coabitação	36.673	49.532	0	42,5%	57,5%	0,0%
	Ônus	174.114	314.269	0	35,7%	64,3%	0,0%
	Déficit	**284.155**	**428.118**	**539**	**39,9%**	**60,1%**	**0,1%**
Centro-Oeste	Precários	41.563	59.054	719	41,0%	58,3%	0,7%
	Coabitação	69.384	59.025	0	54,0%	46,0%	0,0%
	Ônus	124.009	233.360	0	34,7%	65,3%	0,0%
	Déficit	**234.956**	**351.440**	**719**	**40,0%**	**59,9%**	**0,1%**
Brasil	Precários	566.741	666.597	8.100	45,7%	53,7%	0,7%
	Coabitação	430.017	640.423	0	40,2%	59,8%	0,0%
	Ônus	1.278.869	2.386.571	0	34,9%	65,1%	0,0%
	Déficit	**2.275.627**	**3.693.590**	**8.100**	**38,1%**	**61,8%**	**0,1%**
Total das RM	Precários	135.880	178.218	2.610	42,9%	56,3%	0,8%
	Coabitação	163.571	288.395	0	36,2%	63,8%	0,0%
	Ônus	555.059	1.007.345	0	35,5%	64,5%	0,0%
	Déficit	**854.509**	**1.473.958**	**2.610**	**36,7%**	**63,2%**	**0,1%**
Demais áreas	Precários	430.861	488.379	5.490	46,6%	52,8%	0,6%

Especificação	Componente	Total			Composição		
		Homem	Mulher	Ignorado	Homem	Mulher	Ignorado
	Coabitação	266.446	352.028	0	43,1%	56,9%	0,0%
	Ônus	723.811	1.379.226	0	34,4%	65,6%	0,0%
	Déficit	**1.421.118**	**2.219.632**	**5.490**	**39,0%**	**60,9%**	**0,2%**

Fonte: Dados básicos: Instituto Brasileiro de Geografia e Estatística (2024); CadÚnico (2023). Elaboração própria.

A Tabela 8 apresenta as taxas específicas do déficit habitacional por sexo do responsável pelo domicílio. Os dados reforçam a prevalência do déficit habitacional entre os domicílios tendo mulheres como responsáveis, tanto no panorama nacional quanto nos recortes por região geográfica, RM e demais áreas. Destacam-se as regiões Centro-Oeste e Norte, que registram as maiores taxas do país. Esses resultados confirmam a predominância feminina no déficit habitacional.

Tabela 8: Taxas específicas[10] do déficit habitacional (1) por sexo do responsável pelo domicílio, por 1.000 domicílios particulares ocupados, segundo regiões geográficas – Brasil – 2023

Especificação	Taxa específica por 1.000 domicílios particulares ocupados (DPO)	
	Homem	Mulher
Norte	72,08	100,91
Nordeste	55,80	72,66
Sudeste	44,17	74,18
Sul	44,28	65,77
Centro-Oeste	66,31	103,26
Brasil	**51,15**	**76,71**
Total das RMs	*52,48*	*75,31*
Demais áreas	*50,36*	*77,64*

Fonte: Dados básicos: Instituto Brasileiro de Geografia e Estatística (2024); CadÚnico (2023). Elaboração própria.
(1) Exceto unidades domésticas conviventes déficit, já que não é possível identificar o sexo do responsável do futuro domicílio não convivente.

[10] As taxas específicas são calculadas a partir do total de domicílios em situação de déficit por sexo do responsável dividido pelo total de domicílios particulares ocupados, cujo responsável declarou aquele sexo, multiplicados por 1.000.

3.4 **Déficit habitacional por cor/raça do responsável pelo domicílio**

Conforme a Tabela 9, segundo a cor/raça do responsável pelo domicílio, o déficit habitacional está dividido entre parda (2,74 milhões), branca (1,91 milhões), preta (1,19 milhões) e outras (118 mil). Ou seja, os não brancos são responsáveis por 4,05 milhões (67,9% do total) de domicílios em situação de déficit habitacional.

Do ponto de vista regional, o Gráfico 3 mostra o predomínio de pardos como cor/raça do responsável pelo domicílio em todas as regiões brasileiras, com exceção do Sul, onde predomina a população branca, reflexo das desigualdades regionais na composição por cor/raça dos responsáveis pelos domicílios. No Sudeste também se destaca a cor/raça branca, declarada por quase 40% dos responsáveis de domicílio em déficit.

Tabela 9: Déficit habitacional por cor/raça do responsável pelo domicílio, segundo regiões geográficas – Brasil – 2023

(continua)

Especificação	Componente	Cor/raça				
		Branca	Preta	Parda	Outras[1]	Ignorado
Norte	Precários	29.962	171.643	81.365	9.784	2.639
	Coabitação	25.657	26.189	154.303	6.465	0
	Ônus	47.489	28.980	138.294	6.136	0
	Déficit	**103.109**	**226.812**	**373.962**	**22.385**	**2.639**
Nordeste	Precários	66.300	242.556	191.506	8.950	2.889
	Coabitação	50.583	42.569	201.008	1.998	0
	Ônus	183.654	131.130	489.122	22.376	0
	Déficit	**300.537**	**416.256**	**881.636**	**33.323**	**2.889**
Sudeste	Precários	74.221	77.131	39.847	1.613	1.472
	Coabitação	110.295	68.210	159.926	8.108	513
	Ônus	732.239	247.924	761.290	28.695	2.357
	Déficit	**916.755**	**393.265**	**961.063**	**38.416**	**4.341**
Sul	Precários	81.540	14.026	39.758	2.355	546
	Coabitação	51.096	8.404	25.845	860	0
	Ônus	292.768	41.845	149.397	4.374	0
	Déficit	**425.404**	**64.275**	**215.001**	**7.588**	**546**
Centro-Oeste	Precários	28.225	30.361	37.493	4.520	736

Especificação	Componente	Cor/raça				
		Branca	Preta	Parda	Outras[1]	Ignorado
	Coabitação	23.474	24.645	74.988	5.304	0
	Ônus	115.677	38.605	196.262	6.825	0
	Déficit	**167.375**	**93.611**	**308.743**	**16.650**	**736**
Brasil	Precários	280.248	535.717	389.969	27.221	8.282
	Coabitação	261.105	170.018	616.071	22.734	513
	Ônus	1.371.827	488.484	1.734.366	68.406	2.357
	Déficit	**1.913.180**	**1.194.219**	**2.740.405**	**118.361**	**11.151**
Total das RM	Precários	66.928	169.907	71.863	5.306	2.702
	Coabitação	99.976	83.565	258.391	9.521	513
	Ônus	571.146	241.400	721.170	26.330	2.357
	Déficit	**738.050**	**494.873**	**1.051.424**	**41.157**	**5.572**
Demais áreas	Precários	213.320	365.810	318.105	21.915	5.579
	Coabitação	161.128	86.453	357.680	13.213	0
	Ônus	800.681	247.084	1.013.196	42.076	0
	Déficit	**1.175.130**	**699.346**	**1.688.981**	**77.204**	**5.579**

Fonte: Dados básicos: Instituto Brasileiro de Geografia e Estatística (2024); CadÚnico (2023). Elaboração própria.

(1) Soma de amarela e indígena.

Gráfico 3: Composição relativa, por cor/raça do responsável, do déficit habitacional – Brasil – 2023

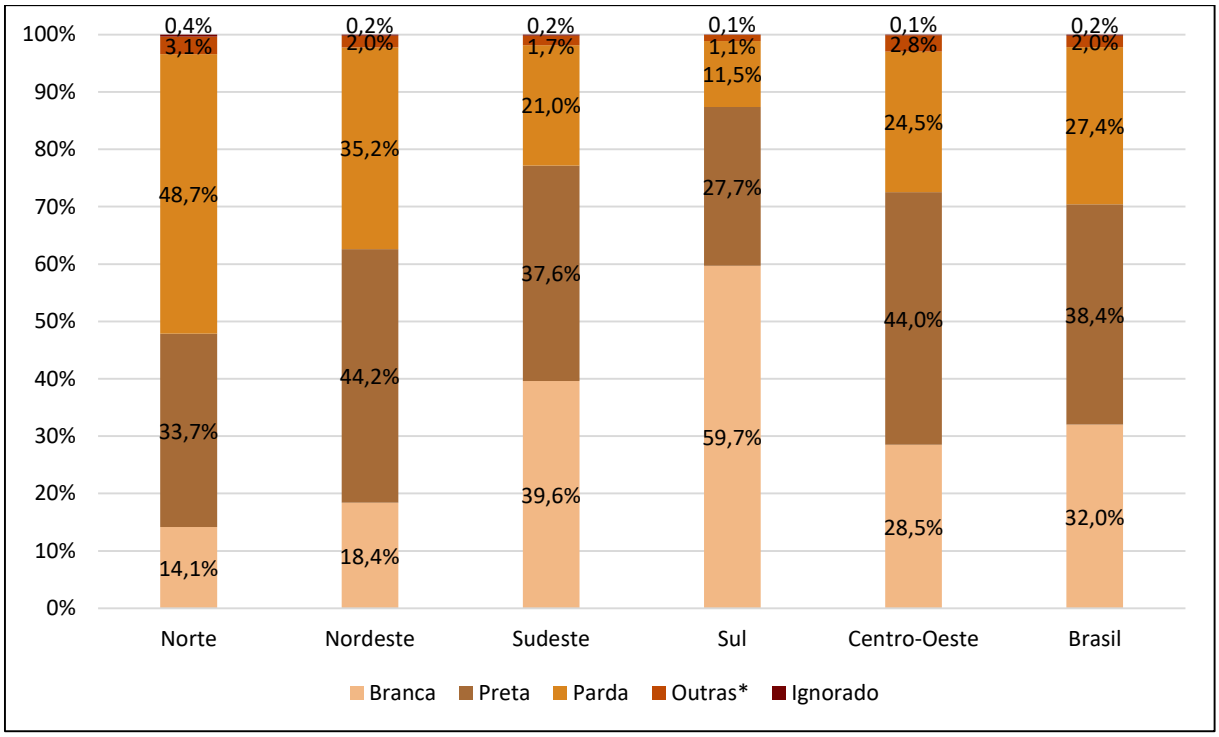

Fonte: Dados básicos: Instituto Brasileiro de Geografia e Estatística (2024); CadÚnico (2023). Elaboração própria.

A Tabela 10, ao cruzar o componente do déficit habitacional com a cor/raça do responsável, evidencia o predomínio de pessoas não brancas em todos os componentes do déficit. Nas regiões Sudeste e Centro-Oeste esse predomínio se destaca principalmente no componente de coabitação. Já nas regiões Norte e Nordeste, o destaque entre os não brancos está também nas habitações precárias. No caso do ônus excessivo com o aluguel urbano, a participação relativa dos brancos é um pouco maior, embora não predominante. A exceção ao descrito anteriormente é a região Sul, onde há predomínio de responsável branco em todos os componentes com quase 60%.

A Tabela 11 apresenta as taxas específicas do déficit habitacional por cor/raça do responsável pelo domicílio. Os dados destacam que o déficit habitacional é mais incidente entre os domicílios por pessoas não-brancas como responsável em todas as regiões do país, incluindo os recortes por RM e demais áreas. Mais especificamente, os domicílios com pessoas pretas e pardas como responsáveis concentram as maiores taxas de déficit habitacional em todas as regiões. Além disso, verifica-se que as regiões Norte e Centro-Oeste apresentam maior prevalência do déficit habitacional em todos os grupos raciais.

Tabela 10: Composição por cor/raça do responsável do déficit habitacional, segundo regiões geográficas – Brasil – 2023

(continua)

Especificação	Componente	Cor/raça				
		Branca	Preta	Parda	Outras[1]	Ignorado
Norte	Precários	10,1%	58,1%	27,5%	3,3%	0,9%
	Coabitação	12,1%	12,3%	72,6%	3,0%	0,0%
	Ônus	21,5%	13,1%	62,6%	2,8%	0,0%
	Déficit	**14,1%**	**31,1%**	**51,3%**	**3,1%**	**0,4%**
Nordeste	Precários	12,9%	47,4%	37,4%	1,7%	0,6%
	Coabitação	17,1%	14,4%	67,9%	0,7%	0,0%
	Ônus	22,2%	15,9%	59,2%	2,7%	0,0%
	Déficit	**18,4%**	**25,5%**	**53,9%**	**2,0%**	**0,2%**
Sudeste	Precários	38,2%	39,7%	20,5%	0,8%	0,8%
	Coabitação	31,8%	19,7%	46,1%	2,3%	0,1%
	Ônus	41,3%	14,0%	42,9%	1,6%	0,1%
	Déficit	**39,6%**	**17,0%**	**41,5%**	**1,7%**	**0,2%**
Sul	Precários	59,0%	10,1%	28,8%	1,7%	0,4%
	Coabitação	59,3%	9,7%	30,0%	1,0%	0,0%
	Ônus	59,9%	8,6%	30,6%	0,9%	0,0%
	Déficit	**59,7%**	**9,0%**	**30,2%**	**1,1%**	**0,1%**
Centro-Oeste	Precários	27,9%	30,0%	37,0%	4,5%	0,7%
	Coabitação	18,3%	19,2%	58,4%	4,1%	0,0%
	Ônus	32,4%	10,8%	54,9%	1,9%	0,0%
	Déficit	**28,5%**	**15,9%**	**52,6%**	**2,8%**	**0,1%**
Brasil	Precários	22,6%	43,2%	31,4%	2,2%	0,7%
	Coabitação	24,4%	15,9%	57,6%	2,1%	0,0%
	Ônus	37,4%	13,3%	47,3%	1,9%	0,1%
	Déficit	**32,0%**	**20,0%**	**45,8%**	**2,0%**	**0,2%**
Total das RM	Precários	21,1%	53,6%	22,7%	1,7%	0,9%
	Coabitação	22,1%	18,5%	57,2%	2,1%	0,1%
	Ônus	36,6%	15,5%	46,2%	1,7%	0,2%
	Déficit	**31,7%**	**21,2%**	**45,1%**	**1,8%**	**0,2%**
Demais áreas	Precários	23,1%	39,6%	34,4%	2,4%	0,6%

Especificação	Componente	Cor/raça				
		Branca	Preta	Parda	Outras(1)	Ignorado
	Coabitação	26,1%	14,0%	57,8%	2,1%	0,0%
	Ônus	38,1%	11,7%	48,2%	2,0%	0,0%
	Déficit	**32,2%**	**19,2%**	**46,3%**	**2,1%**	**0,2%**

Fonte: Dados básicos: Instituto Brasileiro de Geografia e Estatística (2024); CadÚnico (2023). Elaboração própria.
(1) Soma de amarela e indígena.

Tabela 11:Taxas específicas[11] do déficit habitacional (1) por raça/cor do(a) responsável pelo domicílio por 1.000 domicílios particulares ocupados, segundo regiões geográficas – Brasil – 2023

Especificação	Taxa específica por 1.000 domicílios particulares ocupados (DPO)			
	Branca	Parda	Preta	Outra(2)
Norte	70,96	90,32	79,6	128,55
Nordeste	51,97	68,77	67,65	112,08
Sudeste	49,79	68,80	67,83	59,25
Sul	46,25	78,58	74,46	69,20
Centro-Oeste	72,58	89,56	86,1	167,27
Brasil	**51,46**	**73,98**	**70,48**	**90,11**
Total das RMs	*51,88*	*75,04*	*70,57*	*69,58*
Demais áreas	*51,20*	*73,36*	*70,41*	*107,32*

Fonte: Dados básicos: Instituto Brasileiro de Geografia e Estatística (2024); CadÚnico (2023). Elaboração própria.
(1) Exceto unidades domésticas conviventes déficit.
(2) Soma amarela e indígena.

[11] As taxas específicas são calculadas a partir do total de domicílios em situação de déficit por cor ou raça do responsável dividido pelo total de domicílios particulares ocupados, cujo responsável possui aquela cor ou raça multiplicados por 1.000.

4 HABITAÇÃO PRECÁRIA

Conforme a Figura 1 e FJP (2021), a habitação precária é dividida em dois subcomponentes: domicílios improvisados e domicílios rústicos. Os domicílios improvisados, extraídos da base do CadÚnico, são definidos como:

> [...] espaço que, no momento da entrevista, está precariamente adaptado pela família para servir de moradia. Nestes domicílios, geralmente não é possível distinguir cômodos ou individualizar os espaços. Normalmente, não têm acesso a serviços básicos de abastecimento de água, energia elétrica, saneamento ou coleta de lixo, configurando uma situação de extrema vulnerabilidade. Nesses locais, pessoas ou famílias podem fixar moradia, adaptando o espaço às suas necessidades. Os domicílios particulares improvisados podem estar em áreas privadas como prédios ou casas abandonadas, construções, acampamentos em áreas rurais, ou em áreas públicas como barracas, tendas, etc. (Brasil, 2023, p. 44).

Já os domicílios rústicos, construídos a partir da PnadC, são definidos a partir dos materiais precários que predominam na construção das paredes externas do domicílio, especialmente taipa sem revestimento, madeira aproveitada e outros materiais precários.

Como mostrado nas Tabelas 1 e 2 da seção anterior, o componente de habitação precária apresentou uma redução em relação ao ano de 2022, correspondendo atualmente a 20,8% dos domicílios classificados como em situação de déficit habitacional no Brasil. Esse percentual representa um total de 1,24 milhão de domicílios, tornando-se o segundo componente de maior peso no cálculo do déficit. Ademais, em virtude das já mencionadas particularidades regionais, destaca-se que domicílios em situação de habitação precária têm a maior participação no déficit habitacional para as regiões Norte (40,5%) e Nordeste (31,3%), além de terem menor peso nas RM (13,6%) em relação às demais áreas (25,4%). Em conjunto com os dados a seguir, essa exposição inicial permite visualizar como a distribuição geográfica desse componente possui características próprias quando em comparação à dinâmica do indicador geral de déficit habitacional.

4.1 **Habitação precária por situação (urbano e rural)**

Analisando por situação do domicílio, a Tabela 12 mostra que, assim como o indicador geral do déficit habitacional, a habitação precária é observada majoritariamente em domicílios urbanos, sendo que eles representam 60,8% (754 mil) do total desse componente para o Brasil. Todavia, é notável que a participação de domicílios rurais na habitação precária, embora não seja predominante, é expressiva. Seu percentual está acima de 35% no Brasil (39,2%), na região Centro-Oeste (36,6%) e no território fora das RM (49,4%). Por sua vez, a região Nordeste configura-se como

um caso particular, com predomínio da habitação precária em domicílios rurais (56%). Essa proporção, inclusive, foi ampliada em relação ao observado no ano de 2022. Essa característica é observada em quase todas as UFs que compõem essa região. As exceções são Rio Grande do Norte, Paraíba e Alagoas, onde os domicílios rurais representam, respectivamente, 43,6%, 36% e 38,6% de habitação precária.

Assim como a totalidade das RM, as regiões Sudeste e Sul têm para o componente de habitação precária uma distribuição por situação de domicílio similar à observada para o déficit habitacional em geral (Tabela 3). Sua distribuição está concentrada nos territórios urbanos, representando acima de 70% do total e refletindo a maior urbanização dessas regiões.

Por fim, destaca-se que a região Nordeste apresenta os maiores valores absolutos de domicílios em situação de habitação precária (512,2 mil). Fato idêntico ocorre no caso de domicílios urbanos (225,1 mil) e rurais (287,1 mil). No recorte das UFs, chamam atenção Maranhão, Pará e Bahia, com totais acima de 100 mil domicílios em situação de habitação precária.

Tabela 12: Habitação precária por situação de domicílio, segundo regiões geográficas, unidades da Federação e regiões metropolitanas – Brasil – 2023

(continua)

Especificação	Total			Composição	
	Urbano	Rural	Total	Urbano	Rural
Norte	**194.699**	**100.694**	**295.393**	**65,9%**	**34,1%**
Rondônia	11.763	8.355	20.119	58,5%	41,5%
Acre	10.690	4.420	15.111	70,7%	29,3%
Amazonas	68.234	16.224	84.458	80,8%	19,2%
RM Manaus	54.888	8.939	*63.828*	*86,0%*	*14,0%*
Roraima	2.902	2.652	5.554	52,3%	47,7%
Pará	62.342	59.487	121.829	51,2%	48,8%
RM Belém	*20.796*	*661*	*21.457*	*96,9%*	*3,1%*
Amapá	29.640	3.838	33.478	88,5%	11,5%
RM Macapá	*22.771*	*1.194*	*23.965*	*95,0%*	*5,0%*
Tocantins	9.126	5.717	14.844	61,5%	38,5%
Nordeste	**225.130**	**287.071**	**512.201**	**44,0%**	**56,0%**
Maranhão	68.479	123.270	191.749	35,7%	64,3%
RM Grande São Luís	*10.174*	*2.397*	*12.571*	*80,9%*	*19,1%*
Piauí	18.161	34.456	52.617	34,5%	65,5%
Ride Grande Teresina	*2.576*	*5.158*	*7.734*	*33,3%*	*66,7%*

Especificação	Total			Composição	
	Urbano	Rural	Total	Urbano	Rural
Ceará	5.663	16.732	22.396	25,3%	74,7%
RM Fortaleza	*2.339*	*730*	*3.070*	*76,2%*	*23,8%*
Rio Grande do Norte	12.779	9.887	22.666	56,4%	43,6%
RM Natal	*1.980*	*451*	*2.431*	*81,4%*	*18,6%*
Paraíba	17.485	9.836	27.321	64,0%	36,0%
RM João Pessoa	*6.355*	*990*	*7.345*	*86,5%*	*13,5%*
Pernambuco	13.031	14.236	27.267	47,8%	52,2%
RM Recife	*2.876*	*278*	*3.154*	*91,2%*	*8,8%*
Alagoas	22.175	13.955	36.130	61,4%	38,6%
RM Maceió	*11.342*	*594*	*11.936*	*95,0%*	*5,0%*
Sergipe	7.629	6.311	13.940	54,7%	45,3%
RM Aracaju	*4.038*	*1.550*	*5.588*	*72,3%*	*27,7%*
Bahia	59.728	58.388	118.116	50,6%	49,4%
RM Salvador	*11.708*	*1.539*	*13.247*	*88,4%*	*11,6%*
Sudeste	**162.370**	**31.913**	**194.283**	**83,6%**	**16,4%**
Minas Gerais	24.410	11.839	36.249	67,3%	32,7%
RM Belo Horizonte	*4.885*	*381*	*5.266*	*92,8%*	*7,2%*
Espírito Santo	3.335	2.056	5.392	61,9%	38,1%
RM Grande Vitória	*1.748*	*47*	*1.795*	*97,4%*	*2,6%*
Rio de Janeiro	67.226	2.790	70.016	96,0%	4,0%
RM Rio de Janeiro	*61.721*	*687*	*62.408*	*98,9%*	*1,1%*
São Paulo	67.398	15.228	82.626	81,6%	18,4%
RM São Paulo	*38.386*	*1.749*	*40.135*	*95,6%*	*4,4%*
Sul	**108.419**	**29.805**	**138.224**	**78,4%**	**21,6%**
Paraná	44.764	10.983	55.747	80,3%	19,7%
RM Curitiba	*11.461*	*764*	*12.225*	*93,8%*	*6,2%*
Santa Catarina	31.554	10.382	41.936	75,2%	24,8%
RM Florianópolis	*3.629*	*156*	*3.785*	*95,9%*	*4,1%*
Rio Grande do Sul	32.101	8.441	40.542	79,2%	20,8%
RM Porto Alegre	*7.616*	*301*	*7.917*	*96,2%*	*3,8%*
Centro-Oeste	**64.199**	**37.137**	**101.336**	**63,4%**	**36,6%**
Mato Grosso do Sul	7.823	5.146	12.969	60,3%	39,7%
Mato Grosso	40.813	20.798	61.611	66,2%	33,8%

Especificação	Total			Composição	
	Urbano	Rural	Total	Urbano	Rural
RM Vale do Rio Cuiabá	*2.723*	*855*	*3.578*	*76,1%*	*23,9%*
Goiás	13.159	7.580	20.740	63,4%	36,6%
RM Goiânia	*3.087*	*187*	*3.273*	*94,3%*	*5,7%*
Distrito Federal	2.404	3.613	6.016	40,0%	60,0%
Brasil	**754.817**	**486.620**	**1.241.437**	**60,8%**	**39,2%**
Total das RM	*287.064*	*29.494*	*316.707*	*90,6%*	*9,3%*
Demais áreas	*467.753*	*457.126*	*924.730*	*50,6%*	*49,4%*

Fonte: Dados básicos: Instituto Brasileiro de Geografia e Estatística (2024); CadÚnico (2023). Elaboração própria.

4.2 **Subcomponentes da habitação precária: domicílios improvisados e domicílios rústicos**

Passando a discussão para os subcomponentes da habitação precária, é importante esclarecer que o CadÚnico, utilizado no cálculo de domicílios improvisados, tem como unidade de observação as famílias. Todavia, o uso do CadÚnico é necessário pois ele é uma alternativa para a obtenção dessa informação que, como mostrado na Tabela 13, representa parte relevante do componente de habitação precária.

Para o Brasil de forma agregada, contabilizam-se 598,8 mil domicílios classificados como rústicos (48,2%). Já os domicílios improvisados, totalizam 642,6 mil domicílios (51,8%). A predominância de domicílios improvisados é observada apenas nas regiões Norte (64,5%) e Sudeste (66,9%). Em contrapartida, nas regiões Nordeste (50,6%), Centro-Oeste (59,8) e Sul (79,5%), a proporção de domicílios rústicos supera a de improvisados, embora haja variações dessa composição entre as unidades da Federação que compõem essas regiões.

Por fim, em complemento à análise do tópico anterior, destaca-se que a região Nordeste continua apresentando os maiores valores absolutos de domicílios rústicos (259,2 mil) e improvisados (253 mil), evidenciando a relevância do componente de habitação precária nessa região. Entre as unidades da Federação, o Maranhão se sobressai com o maior número de domicílios rústicos (144,4 mil). No que se refere aos domicílios improvisados, os maiores totais são observados no Pará (76,2 mil) e no Amazonas (70,8 mil).

Tabela 13: Habitação precária por subcomponente, segundo regiões geográficas, unidades da Federação e regiões metropolitanas – Brasil – 2023

(continua)

Especificação	Total		Composição	
	Improvisados	Rústicos	Improvisados	Rústicos
Norte	**190.519**	**104.873**	**64,5%**	**35,5%**
Rondônia	7.305	12.814	36,3%	63,7%
Acre	4.694	10.417	31,1%	68,9%
Amazonas	70.830	13.627	83,9%	16,1%
RM Manaus	*54.738*	*9.090*	*85,8%*	*14,2%*
Roraima	2.127	3.428	38,3%	61,7%
Pará	76.175	45.654	62,5%	37,5%
RM Belém	*20.407*	*1.050*	*95,1%*	*4,9%*
Amapá	20.575	12.903	61,5%	38,5%
RM Macapá	*15.541*	*8.424*	*64,8%*	*35,2%*
Tocantins	8.814	6.030	59,4%	40,6%
Nordeste	**252.979**	**259.222**	**49,4%**	**50,6%**
Maranhão	47.339	144.409	24,7%	75,3%
RM Grande São Luís	*9.330*	*3.241*	*74,2%*	*25,8%*
Piauí	31.774	20.842	60,4%	39,6%
Ride Grande Teresina	*1.959*	*5.775*	*25,3%*	*74,7%*
Ceará	5.650	16.745	25,2%	74,8%
RM Fortaleza	*2.026*	*1.044*	*66,0%*	*34,0%*
Rio Grande do Norte	19.302	3.364	85,2%	14,8%
RM Natal	*2.326*	*105*	*95,7%*	*4,3%*
Paraíba	25.419	1.902	93,0%	7,0%
RM João Pessoa	*6.599*	*745*	*89,9%*	*10,1%*
Pernambuco	19.804	7.463	72,6%	27,4%
RM Recife	*1.830*	*1.324*	*58,0%*	*42,0%*
Alagoas	24.314	11.816	67,3%	32,7%
RM Maceió	*5.812*	*6.124*	*48,7%*	*51,3%*
Sergipe	9.553	4.387	68,5%	31,5%
RM Aracaju	*3.218*	*2.370*	*57,6%*	*42,4%*
Bahia	69.823	48.293	59,1%	40,9%
RM Salvador	*10.620*	*2.627*	*80,2%*	*19,8%*

Especificação	Total		Composição	
	Improvisados	Rústicos	Improvisados	Rústicos
Sudeste	**129.970**	**64.313**	**66,9%**	**33,1%**
Minas Gerais	23.765	12.484	65,6%	34,4%
RM Belo Horizonte	*3.216*	*2.050*	*61,1%*	*38,9%*
Espírito Santo	3.023	2.369	56,1%	43,9%
RM Grande Vitória	*873*	*922*	*48,6%*	*51,4%*
Rio de Janeiro	63.720	6.296	91,0%	9,0%
RM Rio de Janeiro	*58.881*	*3.527*	*94,3%*	*5,7%*
São Paulo	39.462	43.165	47,8%	52,2%
RM São Paulo	*24.177*	*15.958*	*60,2%*	*39,8%*
Sul	**28.380**	**109.844**	**20,5%**	**79,5%**
Paraná	9.042	46.705	16,2%	83,8%
RM Curitiba	*1.905*	*10.320*	*15,6%*	*84,4%*
Santa Catarina	5.652	36.283	13,5%	86,5%
RM Florianópolis	*1.820*	*1.965*	*48,1%*	*51,9%*
Rio Grande do Sul	13.685	26.856	33,8%	66,2%
RM Porto Alegre	*3.667*	*4.249*	*46,3%*	*53,7%*
Centro-Oeste	**40.745**	**60.591**	**40,2%**	**59,8%**
Mato Grosso do Sul	10.145	2.824	78,2%	21,8%
Mato Grosso	11.945	49.666	19,4%	80,6%
RM Vale do Rio Cuiabá	*2.420*	*1.158*	*67,6%*	*32,4%*
Goiás	15.904	4.835	76,7%	23,3%
RM Goiânia	*3.273*	*0*	*100,0%*	*0,0%*
Distrito Federal	2.751	3.265	45,7%	54,3%
Brasil	**642.593**	**598.844**	**51,8%**	**48,2%**
Total das RM	*234.640*	*82.067*	*74,1%*	*25,9%*
Demais áreas	*407.953*	*516.777*	*44,1%*	*55,9%*

Fonte: Dados básicos: Instituto Brasileiro de Geografia e Estatística (2024); CadÚnico (2023). Elaboração própria.

5 COABITAÇÃO

O componente de coabitação é composto por dois subcomponentes obtidos a partir da PnadC. Assim, os domicílios classificados como cômodos, ou seja, aqueles situados em habitações como casas de cômodos, cortiços e cabeças de porco, e as unidades domésticas conviventes em situação de déficit, identificadas quando há, simultaneamente, aos menos um núcleo familiar secundário no domicílio e um adensamento superior a dois moradores por dormitório, quando somados resultam no total de domicílios em situação de coabitação.

Em 2023, o componente de coabitação representou 17,9% do déficit habitacional do país, totalizando 1.070.440 domicílios. Conforme demonstrado na Tabela 1 do relatório, sua participação mostra menor variabilidade entre as grandes regiões brasileiras e entre os domicílios situados em RM e os localizados fora delas, com exceção da região Norte. Nessa região, a coabitação representa 29,2% do déficit e, assim como em 2022, revela-se como um componente particularmente expressivo e característico do déficit habitacional. Nas demais regiões, as proporções variam de 12,1% no Sul a 21,9% no Centro-Oeste.

5.1 **Coabitação por situação (urbano e rural)**

Na Tabela 14, observa-se que em 2023, a coabitação manteve-se como um componente majoritariamente urbano do déficit habitacional brasileiro. Cerca de 87% dos domicílios nessa condição estavam localizados em áreas urbanas, padrão que se repete em todas as grandes regiões, com destaque para o Sudeste (96,3%), Sul (91,5%) e Centro-Oeste (95%). A única exceção parcial é o Nordeste, que apresenta maior proporção de coabitação rural (22,9%) e o maior número absoluto de domicílios rurais nessa condição (67.948). Entre os estados, o Pará destaca-se com aproximadamente 29.115 domicílios rurais em coabitação, o maior valor entre as UFs.

No que se refere ao meio urbano, o Sudeste lidera em números absolutos, com 334.342 domicílios coabitados, sendo São Paulo o estado com maior concentração (163.796). A Região Metropolitana de São Paulo, sozinha, responde por mais de 100 mil desses casos, evidenciando o papel dos grandes centros urbanos na formação do déficit. Ainda que menos expressiva em termos percentuais, a coabitação rural continua relevante em estados como Maranhão, Piauí e Sergipe, revelando desigualdades regionais que exigem políticas habitacionais específicas para contextos urbanos e rurais.

Tabela 14: Coabitação por situação de domicílio, segundo regiões geográficas, unidades da Federação e regiões metropolitanas – Brasil – 2023

(continua)

Especificação	Total			Composição	
	Urbano	Rural	**Total**	Urbano	Rural
Norte	**168.386**	**44.228**	**212.614**	**79,2%**	**20,8%**
Rondônia	8.103	1.077	9.180	88,3%	11,7%
Acre	4.943	1.685	6.627	74,6%	25,4%
Amazonas	48.633	9.910	58.543	83,1%	16,9%
RM Manaus	*28.513*	*2.027*	*30.540*	*93,4%*	*6,6%*
Roraima	6.215	589	6.804	91,3%	8,7%
Pará	81.142	29.115	110.257	73,6%	26,4%
RM Belém	*33.561*	*267*	*33.828*	*99,2%*	*0,8%*
Amapá	10.589	980	11.570	91,5%	8,5%
RM Macapá	*8.058*	*0*	*8.058*	*100,0%*	*0,0%*
Tocantins	8.761	872	9.633	90,9%	9,1%
Nordeste	**228.210**	**67.948**	**296.159**	**77,1%**	**22,9%**
Maranhão	35.378	18.466	53.845	65,7%	34,3%
RM Grande São Luís	*12.199*	*212*	*12.411*	*98,3%*	*1,7%*
Piauí	12.141	5.943	18.084	67,1%	32,9%
Ride Grande Teresina	*8.525*	*702*	*9.227*	*92,4%*	*7,6%*
Ceará	35.167	10.771	45.938	76,6%	23,4%
RM Fortaleza	*22.555*	*0*	*22.555*	*100,0%*	*0,0%*
Rio Grande do Norte	18.851	3.542	22.393	84,2%	15,8%
RM Natal	*10.376*	*692*	*11.068*	*93,7%*	*6,3%*
Paraíba	16.945	2.539	19.485	87,0%	13,0%
RM João Pessoa	*10.009*	*105*	*10.114*	*99,0%*	*1,0%*
Pernambuco	33.888	7.187	41.075	82,5%	17,5%
RM Recife	*16.170*	*0*	*16.170*	*100,0%*	*0,0%*
Alagoas	12.827	4.141	16.968	75,6%	24,4%
RM Maceió	*5.514*	*151*	*5.666*	*97,3%*	*2,7%*
Sergipe	5.012	2.174	7.186	69,8%	30,2%
RM Aracaju	*3.390*	*141*	*3.531*	*96,0%*	*4,0%*
Bahia	58.001	13.185	71.186	81,5%	18,5%
RM Salvador	*15.266*	*0*	*15.266*	*100,0%*	*0,0%*

Especificação	Total			Composição	
	Urbano	Rural	**Total**	Urbano	Rural
Sudeste	**334.342**	**12.710**	**347.052**	**96,3%**	**3,7%**
Minas Gerais	70.874	5.280	76.154	93,1%	6,9%
RM Belo Horizonte	*21.730*	*154*	*21.884*	*99,3%*	*0,7%*
Espírito Santo	13.593	1.683	15.277	89,0%	11,0%
RM Grande Vitória	*6.855*	*0*	*6.855*	*100,0%*	*0,0%*
Rio de Janeiro	86.079	531	86.610	99,4%	0,6%
RM Rio de Janeiro	*67.872*	*0*	*67.872*	*100,0%*	*0,0%*
São Paulo	163.796	5.216	169.012	96,9%	3,1%
RM São Paulo	*100.817*	*178*	*100.996*	*99,8%*	*0,2%*
Sul	**78.857**	**7.348**	**86.205**	**91,5%**	**8,5%**
Paraná	27.022	2.010	29.032	93,1%	6,9%
RM Curitiba	*10.964*	*0*	*10.964*	*100,0%*	*0,0%*
Santa Catarina	25.980	1.302	27.282	95,2%	4,8%
RM Florianópolis	*6.614*	*0*	*6.614*	*100,0%*	*0,0%*
Rio Grande do Sul	25.855	4.037	29.891	86,5%	13,5%
RM Porto Alegre	*8.668*	*0*	*8.668*	*100,0%*	*0,0%*
Centro-Oeste	**121.992**	**6.418**	**128.410**	**95,0%**	**5,0%**
Mato Grosso do Sul	15.265	638	15.903	96,0%	4,0%
Mato Grosso	25.998	3.469	29.467	88,2%	11,8%
RM Vale do Rio Cuiabá	*14.389*	*861*	*15.250*	*94,4%*	*5,6%*
Goiás	65.931	1.065	66.996	98,4%	1,6%
RM Goiânia	*34.430*	*0*	*34.430*	*100,0%*	*0,0%*
Distrito Federal	14.798	1.246	16.043	92,2%	7,8%
Brasil	**931.788**	**138.652**	**1.070.440**	**87,0%**	**13,0%**
Total das RM	*446.473*	*5.493*	*451.966*	*98,8%*	*1,2%*
Demais áreas	*485.314*	*133.160*	*618.474*	*78,5%*	*21,5%*

Fonte: Dados básicos: Instituto Brasileiro de Geografia e Estatística (2024).
Elaboração própria.

5.2 Subcomponentes da coabitação: cômodos e unidade convivente déficit

A Tabela 15 apresenta os subcomponentes da coabitação. É possível notar que a categoria de unidade convivente déficit representou 86,6% do total do componente, enquanto os cômodos — moradias em casas de cômodos, cortiços e semelhantes — corresponderam a 13,4%. A predominância do subcomponente de unidade convivente déficit ainda é observada, com pequenas variações, em quase todas as regiões e unidades da Federação. O Centro-Oeste, por sua vez, é uma exceção ao padrão, a distribuição entre os dois subcomponentes é quase idêntica, com os cômodos em 50,5% dos casos. Em Goiás, por exemplo, os dados demonstram uma situação única, na qual 73,2% das coabitações ocorrem em cômodos.

Tabela 15: Coabitação por subcomponente, segundo regiões geográficas, unidades da Federação e regiões metropolitanas – Brasil – 2023

(continua)

Especificação	Total		Composição	
	Cômodos	Unidade convivente déficit	Cômodos	Unidade convivente déficit
Norte	**15.370**	**197.244**	**7,2%**	**92,8%**
Rondônia	1.363	7.817	14,8%	85,2%
Acre	0	6.627	0,0%	100,0%
Amazonas	2.841	55.701	4,9%	95,1%
RM Manaus	*2.468*	*28.072*	*8,1%*	*91,9%*
Roraima	738	6.066	10,8%	89,2%
Pará	6.337	103.920	5,7%	94,3%
RM Belém	*1.615*	*32.214*	*4,8%*	*95,2%*
Amapá	1.008	10.562	8,7%	91,3%
RM Macapá	*789*	*7.269*	*9,8%*	*90,2%*
Tocantins	3.082	6.550	32,0%	68,0%
Nordeste	**14.742**	**281.417**	**5,0%**	**95,0%**
Maranhão	3.796	50.049	7,0%	93,0%
RM Grande São Luís	*2.231*	*10.180*	*18,0%*	*82,0%*
Piauí	1.321	16.763	7,3%	92,7%
Ride Grande Teresina	*1.215*	*8.013*	*13,2%*	*86,8%*
Ceará	711	45.227	1,5%	98,5%
RM Fortaleza	*711*	*21.843*	*3,2%*	*96,8%*

Especificação	Total		Composição	
	Cômodos	Unidade convivente déficit	Cômodos	Unidade convivente déficit
Rio Grande do Norte	0	22.393	0,0%	100,0%
RM Natal	*0*	*11.068*	*0,0%*	*100,0%*
Paraíba	3.420	16.064	17,6%	82,4%
RM João Pessoa	*2.142*	*7.972*	*21,2%*	*78,8%*
Pernambuco	2.008	39.067	4,9%	95,1%
RM Recife	*0*	*16.170*	*0,0%*	*100,0%*
Alagoas	919	16.049	5,4%	94,6%
RM Maceió	*0*	*5.666*	*0,0%*	*100,0%*
Sergipe	0	7.186	0,0%	100,0%
RM Aracaju	*0*	*3.531*	*0,0%*	*100,0%*
Bahia	2.566	68.619	3,6%	96,4%
RM Salvador	*260*	*15.006*	*1,7%*	*98,3%*
Sudeste	**41.796**	**305.256**	**12,0%**	**88,0%**
Minas Gerais	9.506	66.647	12,5%	87,5%
RM Belo Horizonte	*661*	*21.223*	*3,0%*	*97,0%*
Espírito Santo	1.809	13.468	11,8%	88,2%
RM Grande Vitória	*420*	*6.434*	*6,1%*	*93,9%*
Rio de Janeiro	16.086	70.523	18,6%	81,4%
RM Rio de Janeiro	*15.507*	*52.365*	*22,8%*	*77,2%*
São Paulo	14.394	154.618	8,5%	91,5%
RM São Paulo	*10.248*	*90.748*	*10,1%*	*89,9%*
Sul	**6.692**	**79.513**	**7,8%**	**92,2%**
Paraná	0	29.032	0,0%	100,0%
RM Curitiba	*0*	*10.964*	*0,0%*	*100,0%*
Santa Catarina	5.939	21.342	21,8%	78,2%
RM Florianópolis	*2.287*	*4.327*	*34,6%*	*65,4%*
Rio Grande do Sul	753	29.139	2,5%	97,5%
RM Porto Alegre	*341*	*8.327*	*3,9%*	*96,1%*
Centro-Oeste	**64.787**	**63.623**	**50,5%**	**49,5%**
Mato Grosso do Sul	2.492	13.411	15,7%	84,3%
Mato Grosso	11.070	18.397	37,6%	62,4%
RM Vale do Rio Cuiabá	*10.018*	*5.232*	*65,7%*	*34,3%*

Especificação	Total		Composição	
	Cômodos	Unidade convivente déficit	Cômodos	Unidade convivente déficit
Goiás	49.043	17.953	73,2%	26,8%
RM Goiânia	*27.637*	*6.793*	*80,3%*	*19,7%*
Distrito Federal	2.181	13.862	13,6%	86,4%
Brasil	**143.387**	**927.052**	**13,4%**	**86,6%**
Total das RM	*78.550*	*373.416*	*17,4%*	*82,6%*
Demais áreas	*64.837*	*553.637*	*10,5%*	*89,5%*

Fonte: Dados básicos: Instituto Brasileiro de Geografia e Estatística (2024).
Elaboração própria.

6 ÔNUS EXCESSIVO COM O ALUGUEL URBANO

O ônus excessivo com o aluguel urbano é um componente importante para captar o acesso à habitação pelas famílias. Ele ocorre em domicílios urbanos com até três SM de renda domiciliar e cujo gasto com o aluguel supere 30% da sua renda, podendo resultar em dificuldades financeiras, perda de bem-estar e instabilidade habitacional devido à maior propensão de despejo. Dessa forma, a integração desse componente no cálculo do déficit habitacional é fundamental, especialmente entre os domicílios de baixa renda.

Como mencionado na primeira parte deste relatório, a Tabela 1 evidencia a expressividade do ônus excessivo com o aluguel urbano para o déficit habitacional no Brasil, sendo este o de maior proporção no déficit, mas também mostra que há especificidades entre as regiões. Ele é responsável por mais da metade do déficit habitacional nacional (61,3%) e é o principal contribuinte do déficit em todas as regiões, com exceção do Norte.

Outra observação importante é que 48,3% do ônus está concentrado na região Sudeste, impulsionado por São Paulo, que, sozinho, contribui para 26,4% do ônus no Brasil. Em seguida, vem Rio de Janeiro e Minas Gerais com 10,3% e 10% respectivamente. Em termos absolutos, Amapá, Acre e Roraima são os estados com menor número. Em relação à participação do ônus no déficit, Amapá (11,3%), Maranhão (19,6%) e Piauí (22,5%) possuem os menores valores, enquanto Distrito Federal (79,4%), São Paulo (79,4%) e Minas Gerais (76,5%) os maiores. De modo geral, o padrão de concentração do ônus excessivo com aluguel urbano por unidades da Federação manteve-se semelhante ao observado nos dados de 2022.

Além do mais, o ônus excessivo com aluguel urbano é o principal componente do déficit nas RMs, sendo responsável por 67% do déficit habitacional, ao passo que nas demais áreas é de 57,7%, uma vez que as habitações precárias também possuem um peso expressivo (Tabela 2). Por outro lado, em termos absolutos, o ônus excessivo com aluguel urbano no Brasil não se concentra nas RMs, mas sim nas demais áreas (Tabela 1). Dos 3.665.440 domicílios em situação de ônus, 1.562.404 estão nas RMs e 2.103.036 estão nas demais áreas.

Em comparação com 2022, houve um aumento no número de domicílios em situação de ônus excessivo com aluguel urbano no Brasil. O total passou de 3.242.780 para 3.665.440, representando um crescimento de aproximadamente 13%. Esse aumento foi observado tanto nas RMs quanto nas demais áreas: nas RMs, o número subiu de 1.437.006 para 1.562.404 domicílios (+8,7%), enquanto fora delas o salto foi de 1.805.774 para 2.103.036 domicílios (+16,5%).

6.1 Ônus excessivo com o aluguel urbano por arranjo domiciliar

Uma análise interessante em relação ao ônus excessivo com aluguel urbano é fazê-la conforme o arranjo domiciliar. Mesmo com a prevalência do arranjo domiciliar de casal com filhos, tem crescido o número de domicílios monoparentais, especialmente aqueles que têm como responsável uma mulher (Benatti *et al.*, 2021; Wajnman, 2012). No entanto, muitas vezes, no Brasil, os domicílios monoparentais estão associados à maior vulnerabilidade econômica, uma vez que existe apenas um provedor, enquanto, nos arranjos de casais, a renda domiciliar pode ser complementada entre responsável e cônjuge (Benatti *et al*., 2021).

Ao desagregar os domicílios nucleares de acordo com a presença de cônjuge, o sexo do responsável pelo domicílio e a presença ou não de filho, os maiores valores absolutos são para casais com filhos (718.286 domicílios) e monoparentais, tendo uma mulher como responsável e todos os filhos menores de 18 anos (684.341 domicílios) — ver Gráfico 4. Os valores dos unipessoais também são expressivos, para responsável mulher (591.834) e homem (575.543), e, em seguida, outros arranjos (435.754) que envolvem predominantemente domicílios estendidos e compostos[12].

[12] Os domicílios nucleares se limitam àqueles em que as relações familiares no domicílio são entre cônjuges e entre pais e filhos. Já os domicílios estendidos incluem, além destes, outros parentes corresidentes. Por fim, os domicílios compostos incluem não parentes corresidentes (Wajnman, 2012).

Gráfico 4: Ônus excessivo com aluguel urbano por arranjo domiciliar – famílias nucleares, unipessoais e outros (estendidos e compostos) – Brasil – 2023

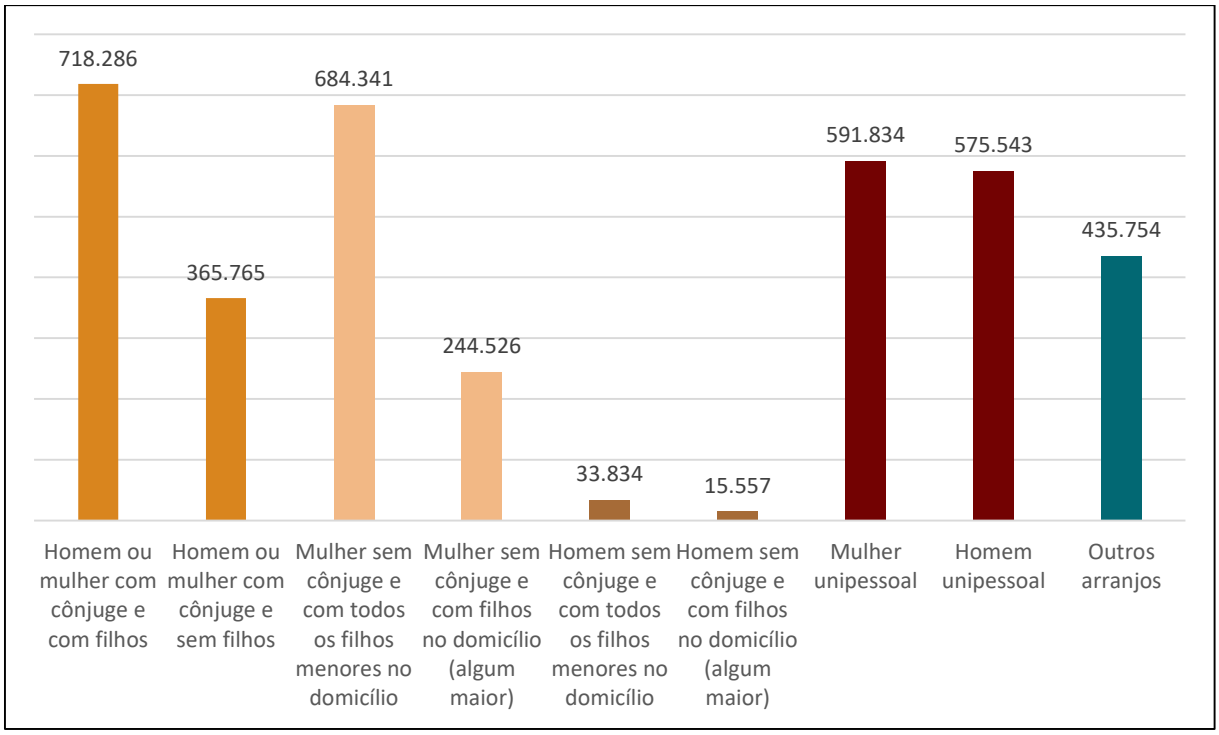

Fonte: Dados básicos: Instituto Brasileiro de Geografia e Estatística (2024).
Elaboração própria.

Contudo, em termos relativos, são os domicílios monoparentais que possuem uma mulher como responsável e todos os filhos menores de 18 anos (49,1%) e os domicílios unipessoais femininos (55,8%) que possuem maiores proporções de ônus excessivo com o aluguel dentro do total de domicílios do arranjo em questão. Em outras palavras, são esses dois arranjos domiciliares que teriam maior probabilidade de incidência de ônus — ver Gráfico 5.

Embora os valores absolutos do ônus tenham aumentado entre 2022 e 2023 para todos os arranjos, verifica-se que em termos percentuais — ou seja, a taxa de incidência — a maioria apresentou queda em relação ao ano de 2019. Duas exceções, no entanto, merecem destaque: o arranjo monoparental tendo um homem como responsável e todos os filhos menores de idade, que passou de 38,6% em 2019 para 40,8% em 2023, indicando um agravamento relativo nesse grupo; e o arranjo monoparental tendo um homem como responsável e com filhos no domicílio — algum maior de 18 anos — que, apesar de ter registrado uma queda acentuada em 2022 (de 23,1% para 12,9%), voltou a crescer em 2023, superando os níveis de 2019 ao atingir 24%.

Gráfico 5: Comparação do ônus excessivo com aluguel urbano relativo por arranjo domiciliar[1] – famílias nucleares, unipessoais e outros (estendidos e compostos) – Brasil – 2019/2022/2023

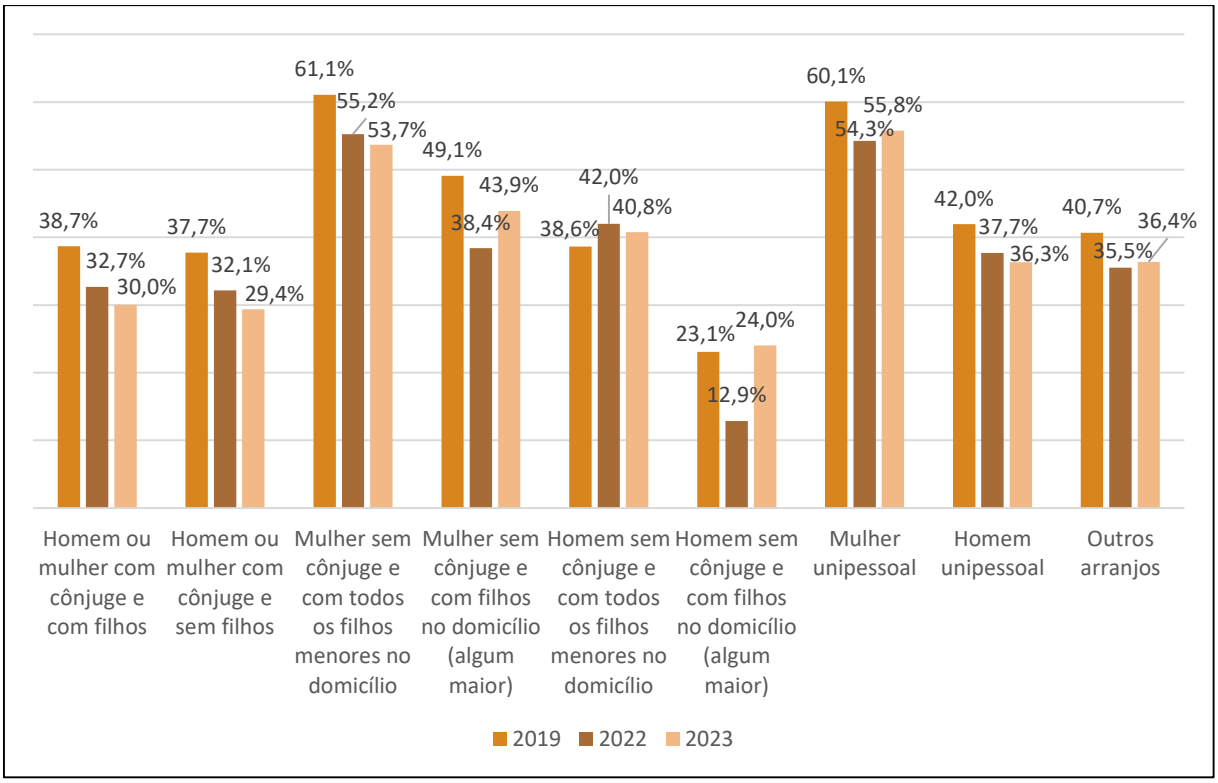

Fonte: Dados básicos: Instituto Brasileiro de Geografia e Estatística (2024).
Elaboração própria.
(1) Percentual do total de domicílios com o respectivo arranjo domiciliar urbano que paga aluguel e com renda de até três salários mínimos.

6.2 Domicílios em ônus excessivo com aluguel urbano e com alguma inadequação

Nesta seção, serão analisados os domicílios em situação de ônus excessivo com aluguel urbano e nos quais foram identificados, conjuntamente, alguma inadequação de domicílio. Em outras palavras, serão abordados os domicílios em que um dos componentes do déficit quantitativo — o ônus, quando um domicílio gasta mais de 30% da sua renda com o aluguel — se sobrepõe ao déficit qualitativo — inadequação de infraestrutura urbana e/ou inadequação edilícia.

Inicialmente, vale destacar algumas questões metodológicas. Primeiro: não é possível a sobreposição do ônus excessivo com aluguel urbano com o componente de inadequação fundiária, já que ele requer que o domicílio seja próprio e no ônus o domicílio é necessariamente alugado. Segundo: a metodologia de cálculo dos dois indicadores — déficit habitacional e inadequação de domicílios — possibilita que a inadequação se sobreponha apenas aos domicílios em ônus, uma vez que ela se

restringe aos domicílios duráveis urbanos (FJP, 2021). Dessa maneira, no caso do cálculo da inadequação, são excluídos os domicílios classificados como habitação precária — rústicos e improvisados —, cômodos e aqueles situados em áreas rurais. Portanto, nesse caso, um domicílio em ônus excessivo com aluguel urbano pode apresentar, simultaneamente, inadequações, mas essa relação não se aplica aos demais subcomponentes do déficit habitacional.

A Tabela 16 expõe o total de domicílios com ônus excessivo com aluguel urbano; os domicílios com ônus e que também possuem alguma inadequação — de infraestrutura e/ou edilícia — , além do percentual que representam; e os domicílios com ônus sem identificação de inadequação, e a percentagem que representam. Observa-se que na maior parte dos domicílios com ônus excessivo com aluguel no Brasil não foram identificadas inadequações (63,8%). Entretanto, ainda assim, em número absoluto, é um valor expressivo de domicílios que acumulam os dois problemas. Mais de 1 milhão de domicílios são acometidos simultaneamente pelo ônus excessivo com aluguel e pela presença de ao menos uma inadequação, sendo Nordeste e Sudeste as regiões que possuem as maiores quantidades de domicílios em situação de ônus que são inadequados, 433.900 e 400.338, respectivamente — ver Tabela 16.

Tabela 16: Domicílios duráveis urbanos ocupados com ônus excessivo com aluguel urbano e inadequação, segundo regiões geográficas, unidades da Federação e regiões metropolitanas – Brasil – 2023

(continua)

Especificação	Domicílios com ônus		%		Total de domicílios com ônus excessivo com aluguel urbano
	Com alguma inadequação	Sem identificação de inadequação	Com alguma inadequação	Sem dentificação de inadequação	
Norte	**159.714**	**61.185**	**72,3%**	**27,7%**	**220.900**
Rondônia	16.217	10.970	59,6%	40,4%	27.187
Acre	6.183	2.971	67,5%	32,5%	9.155
Amazonas	*31.315*	*16.767*	65,1%	34,9%	*48.082*
RM Manaus	25.433	16.289	*61,0%*	*39,0%*	41.722
Roraima	*13.209*	*1.191*	91,7%	8,3%	*14.400*
Pará	75.051	19.611	79,3%	20,7%	94.662
RM Belém	*25.629*	*9.608*	*72,7%*	*27,3%*	*35.237*
Amapá	5.402	348	93,9%	6,1%	5.751
RM Macapá	4.637	110	*97,7%*	*2,3%*	4.746
Tocantins	12.336	9.327	56,9%	43,1%	21.663

Especificação	Domicílios com ônus		%		Total de domicílios com ônus excessivo com aluguel urbano
	Com alguma inadequação	Sem identificação de inadequação	Com alguma inadequação	Sem dentificação de inadequação	
Nordeste	**433.900**	**392.382**	**52,5%**	**47,5%**	**826.282**
Maranhão	38.954	20.939	65,0%	35,0%	59.893
RM Grande São Luís	*14.926*	*15.596*	*48,9%*	*51,1%*	*30.523*
Piauí	12.791	7.730	62,3%	37,7%	20.521
Ride Grande Teresina	*4.815*	*3.372*	*58,8%*	*41,2%*	*8.187*
Ceará	59.087	84.052	41,3%	58,7%	143.139
RM Fortaleza	*34.414*	*43.907*	*43,9%*	*56,1%*	*78.322*
Rio Grande do Norte	23.231	31.334	42,6%	57,4%	54.565
RM Natal	*8.710*	*22.376*	*28,0%*	*72,0%*	*31.086*
Paraíba	30.307	24.892	54,9%	45,1%	55.199
RM João Pessoa	*10.729*	*12.525*	*46,1%*	*53,9%*	*23.254*
Pernambuco	125.635	64.117	66,2%	33,8%	189.753
RM Recife	*59.854*	*32.494*	*64,8%*	*35,2%*	*92.347*
Alagoas	38.099	18.182	67,7%	32,3%	56.281
RM Maceió	*18.497*	*14.000*	*56,9%*	*43,1%*	*32.498*
Sergipe	27.487	16.010	63,2%	36,8%	43.496
RM Aracaju	*13.686*	*13.599*	*50,2%*	*49,8%*	*27.285*
Bahia	78.309	125.126	38,5%	61,5%	203.435
RM Salvador	*27.203*	*50.032*	*35,2%*	*64,8%*	*77.234*
Sudeste	**400.338**	**1.372.168**	**22,6%**	**77,4%**	**1.772.506**
Minas Gerais	48.787	317.567	13,3%	86,7%	366.353
RM Belo Horizonte	*13.185*	*75.301*	*14,9%*	*85,1%*	*88.486*
Espírito Santo	9.434	49.098	16,1%	83,9%	58.533
RM Grande Vitória	*6.464*	*27.602*	*19,0%*	*81,0%*	*34.066*
Rio de Janeiro	132.377	246.961	34,9%	65,1%	379.339
RM Rio de Janeiro	*97.094*	*174.181*	*35,8%*	*64,2%*	*271.275*
São Paulo	209.740	758.541	21,7%	78,3%	968.281
RM São Paulo	*99.200*	*365.070*	*21,4%*	*78,6%*	*464.271*
Sul	**201.056**	**287.327**	**41,2%**	**58,8%**	**488.383**
Paraná	61.988	127.343	32,7%	67,3%	189.332
RM Curitiba	*13.067*	*47.668*	*21,5%*	*78,5%*	*60.735*

Especificação	Domicílios com ônus		%		Total de domicílios com ônus excessivo com aluguel urbano
	Com alguma inadequação	Sem identificação de inadequação	Com alguma inadequação	Sem identificação de inadequação	
Santa Catarina	43.867	106.706	29,1%	70,9%	150.573
RM Florianópolis	*9.512*	*21.193*	*31,0%*	*69,0%*	*30.705*
Rio Grande do Sul	95.201	53.278	64,1%	35,9%	148.479
RM Porto Alegre	*29.724*	*20.056*	*59,7%*	*40,3%*	*49.781*
Centro-Oeste	**132.104**	**225.266**	**37,0%**	**63,0%**	**357.369**
Mato Grosso do Sul	22.017	31.701	41,0%	59,0%	53.718
Mato Grosso	28.421	45.777	38,3%	61,7%	74.198
RM Vale do Rio Cuiabá	*6.846*	*9.680*	*41,4%*	*58,6%*	*16.526*
Goiás	51.835	92.729	35,9%	64,1%	144.565
RM Goiânia	*20.186*	*43.932*	*31,5%*	*68,5%*	*64.118*
Distrito Federal	29.830	55.058	35,1%	64,9%	84.889
Brasil	**1.327.112**	**2.338.328**	**36,2%**	**63,8%**	**3.665.440**
Total RM	*543.811*	*1.018.592*	*34,8%*	*65,2%*	*1.562.404*
Fora das RM	*783.301*	*1.319.736*	*37,2%*	*62,8%*	*2.103.036*

Fonte: Dados básicos: Instituto Brasileiro de Geografia e Estatística (2024).
Elaboração própria.

Regionalmente, há uma diferença grande entre a composição dos domicílios em ônus com relação a ter ou não a identificação de alguma inadequação — ver Tabela 16 e Mapa 6. Na região Norte, 72,3% dos domicílios em ônus contam com pelo menos alguma inadequação, destacando-se Roraima e Amapá com mais de 90%. Em seguida, tem-se as regiões Nordeste (52,5%) e Sul (41,2%). Por outro lado, nas regiões Sudeste e Centro-Oeste as percentagens são bem inferiores, de 22,6% e 37%. Esses percentuais foram ilustradas no Mapa 6. Ou seja, especialmente no Norte, predominam domicílios em ônus e com inadequação concomitantemente, o que deve ser ponderado nas discussões sobre a questão habitacional no Brasil.

Mapa 6: Proporção de domicílios com ônus e inadequação em relação ao total de domicílios com ônus excessivo com aluguel urbano, segundo unidades da Federação – Brasil – 2023

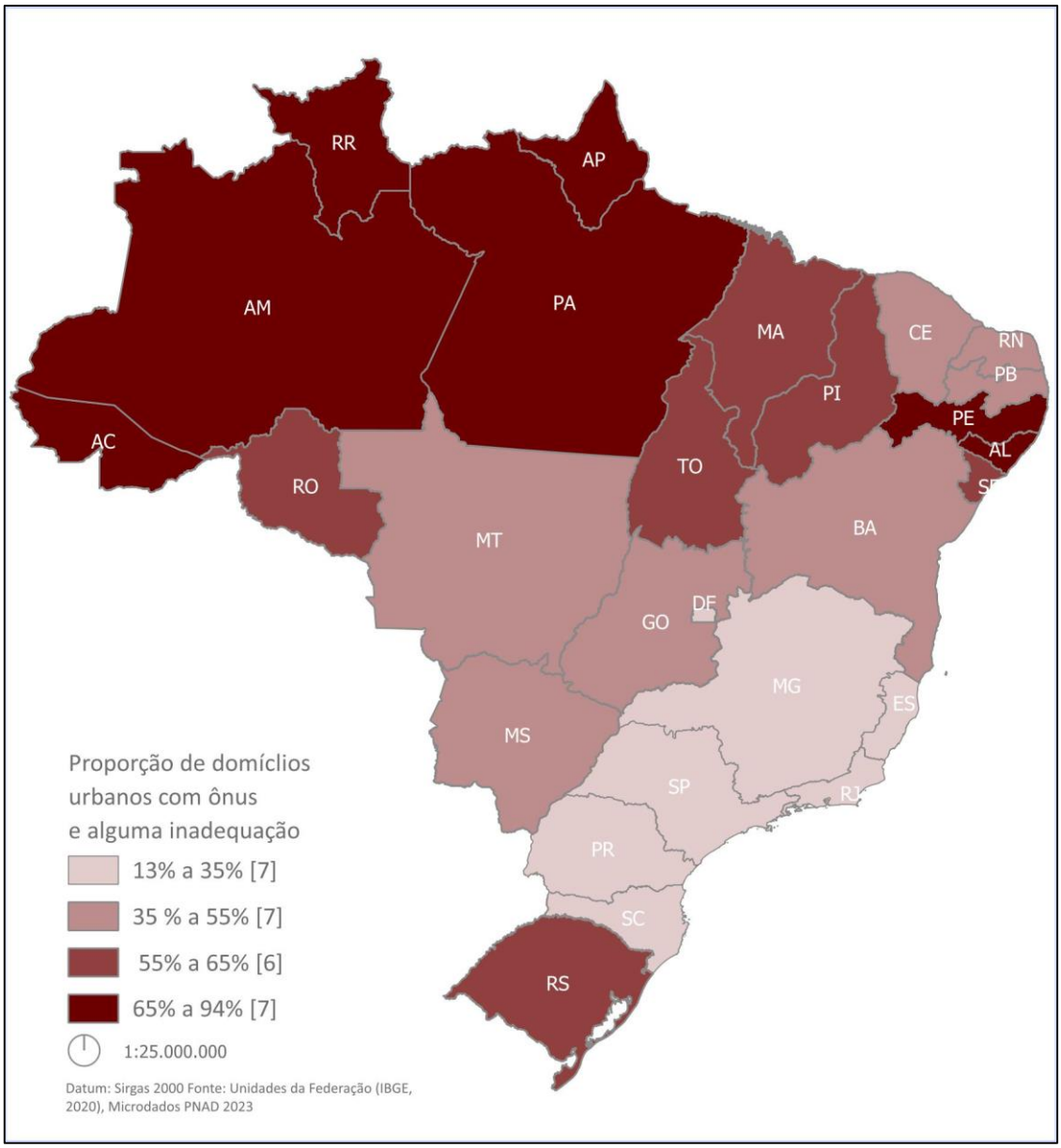

Fonte: Dados básicos: Instituto Brasileiro de Geografia e Estatística (2024).
Elaboração própria.

Além dessa análise geral da sobreposição do ônus e alguma inadequação — de infraestrutura urbana e/ou edilícia —, analisou-se os domicílios com ônus e com cada um dos componentes da inadequação de domicílios separadamente, isto é, com alguma inadequação de infraestrutura urbana e, em um segundo momento, com alguma inadequação edilícia.

6.2.1 Ônus excessivo com aluguel urbano e inadequação de infraestrutura urbana

Ao segmentar a sobreposição do ônus excessivo e, especificamente, da inadequação de infraestrutura urbana, tem-se 740.962 domicílios nessa situação no Brasil, que representam 20,2% do total de domicílios em ônus — ver Tabela 17. Pernambuco destaca-se com o maior valor absoluto (114.308 domicílios), seguido do Rio de Janeiro (106.845 domicílios).

Já em relação às percentagens, mais uma vez os maiores valores estão concentrados nas unidades da Federação das regiões Norte e Nordeste, com exceção de Roraima que é de 10,9% — ver Tabela 17 e Mapa 7. Assim, no Acre e em Pernambuco, por exemplo, 60% dos domicílios que gastam mais de 30% da renda domiciliar com aluguel, ou seja, que estão em ônus, também contam com alguma inadequação no abastecimento de água e/ou no esgotamento sanitário e/ou na coleta do lixo e/ou no abastecimento e/ou frequência de energia elétrica — isto é, nos subcomponentes da inadequação de infraestrutura urbana. Por outro lado, nas unidades da Federação do Sul e do Sudeste essa percentagem é bem inferior, por volta dos 10%, atingindo um máximo de 28,2% no Rio de Janeiro.

Tabela 17: Domicílios duráveis urbanos ocupados com inadequação de infraestrutura urbana e ônus excessivo com aluguel urbano, segundo regiões geográficas, unidades da Federação e regiões metropolitanas – Brasil – 2023

(continua)

Especificação	Domicílios com ônus		%		Total de domicílios com ônus excessivo com aluguel urbano
	Com inadequação de infraestrutura	Sem inadequação de infraestrutura	Com inadequação de infraestrutura	Sem inadequação de infraestrutura	
Norte	**104.538**	**116.361**	**47,3%**	**52,7%**	**220.900**
Rondônia	13.741	13.446	50,5%	49,5%	27.187
Acre	5.519	3.636	60,3%	39,7%	9.155
Amazonas	*20.154*	*27.927*	41,9%	58,1%	*48.082*
RM Manaus	14.649	27.073	*35,1%*	*64,9%*	41.722
Roraima	*1.564*	*12.836*	10,9%	89,1%	*14.400*
Pará	52.880	41.782	55,9%	44,1%	94.662
RM Belém	*10.342*	*24.895*	*29,3%*	*70,7%*	*35.237*
Amapá	3.359	2.391	58,4%	41,6%	5.751
RM Macapá	3.026	1.721	*63,7%*	*36,3%*	4.746
Tocantins	7.321	14.342	33,8%	66,2%	21.663

Especificação	Domicílios com ônus		%		Total de domicílios com ônus excessivo com aluguel urbano
	Com inadequação de infraestrutura	Sem inadequação de infraestrutura	Com inadequação de infraestrutura	Sem inadequação de infraestrutura	
Nordeste	**314.040**	**512.242**	**38,0%**	**62,0%**	**826.282**
Maranhão	28.005	31.888	46,8%	53,2%	59.893
RM Grande São Luís	*10.501*	*20.022*	*34,4%*	*65,6%*	*30.523*
Piauí	5.519	15.002	26,9%	73,1%	20.521
Ride Grande Teresina	*225*	*7.962*	*2,7%*	*97,3%*	*8.187*
Ceará	33.012	110.127	23,1%	76,9%	143.139
RM Fortaleza	*13.796*	*64.525*	*17,6%*	*82,4%*	*78.322*
Rio Grande do Norte	20.725	33.840	38,0%	62,0%	54.565
RM Natal	*6.771*	*24.315*	*21,8%*	*78,2%*	*31.086*
Paraíba	14.364	40.835	26,0%	74,0%	55.199
RM João Pessoa	*3.937*	*19.318*	*16,9%*	*83,1%*	*23.254*
Pernambuco	114.308	75.445	60,2%	39,8%	189.753
RM Recife	*55.287*	*37.060*	*59,9%*	*40,1%*	*92.347*
Alagoas	29.251	27.030	52,0%	48,0%	56.281
RM Maceió	*13.375*	*19.123*	*41,2%*	*58,8%*	*32.498*
Sergipe	18.158	25.338	41,7%	58,3%	43.496
RM Aracaju	*6.358*	*20.927*	*23,3%*	*76,7%*	*27.285*
Bahia	50.699	152.736	24,9%	75,1%	203.435
RM Salvador	*11.584*	*65.650*	*15,0%*	*85,0%*	*77.234*
Sudeste	**213.127**	**1.559.379**	**12,0%**	**88,0%**	**1.772.506**
Minas Gerais	37.931	328.422	10,4%	89,6%	366.353
RM Belo Horizonte	*8.389*	*80.098*	*9,5%*	*90,5%*	*88.486*
Espírito Santo	6.944	51.588	11,9%	88,1%	58.533
RM Grande Vitória	*5.028*	*29.038*	*14,8%*	*85,2%*	*34.066*
Rio de Janeiro	106.845	272.493	28,2%	71,8%	379.339
RM Rio de Janeiro	*76.816*	*194.459*	*28,3%*	*71,7%*	*271.275*
São Paulo	61.406	906.875	6,3%	93,7%	968.281
RM São Paulo	*39.488*	*424.783*	*8,5%*	*91,5%*	*464.271*
Sul	**51.723**	**436.660**	**10,6%**	**89,4%**	**488.383**
Paraná	21.905	167.427	11,6%	88,4%	189.332

Especificação	Domicílios com ônus		%		Total de domicílios com ônus excessivo com aluguel urbano
	Com inadequação de infraestrutura	Sem inadequação de infraestrutura	Com inadequação de infraestrutura	Sem inadequação de infraestrutura	
RM Curitiba	*1.404*	*59.331*	*2,3%*	*97,7%*	*60.735*
Santa Catarina	14.751	135.821	9,8%	90,2%	150.573
RM Florianópolis	*5.675*	*25.030*	*18,5%*	*81,5%*	*30.705*
Rio Grande do Sul	15.067	133.412	10,1%	89,9%	148.479
RM Porto Alegre	*2.439*	*47.342*	*4,9%*	*95,1%*	*49.781*
Centro-Oeste	**57.534**	**299.835**	**16,1%**	**83,9%**	**357.369**
Mato Grosso do Sul	8.490	45.228	15,8%	84,2%	53.718
Mato Grosso	16.165	58.034	21,8%	78,2%	74.198
RM Vale do Rio Cuiabá	*3.994*	*12.531*	*24,2%*	*75,8%*	*16.526*
Goiás	31.036	113.529	21,5%	78,5%	144.565
RM Goiânia	*8.320*	*55.798*	*13,0%*	*87,0%*	*64.118*
Distrito Federal	1.843	83.045	2,2%	97,8%	84.889
Brasil	**740.962**	**2.924.478**	**20,2%**	**79,8%**	**3.665.440**
Total RM	*301.403*	*1.261.001*	*19,3%*	*80,7%*	*1.562.404*
Fora das RM	*439.559*	*1.663.477*	*20,9%*	*79,1%*	*2.103.036*

Fonte: Dados básicos: Instituto Brasileiro de Geografia e Estatística (2024).
Elaboração própria.

Mapa 7: Proporção de domicílios com ônus e inadequação de infraestrutura urbana em relação ao total de domicílios com ônus excessivo com aluguel urbano, segundo unidades da Federação – Brasil – 2023

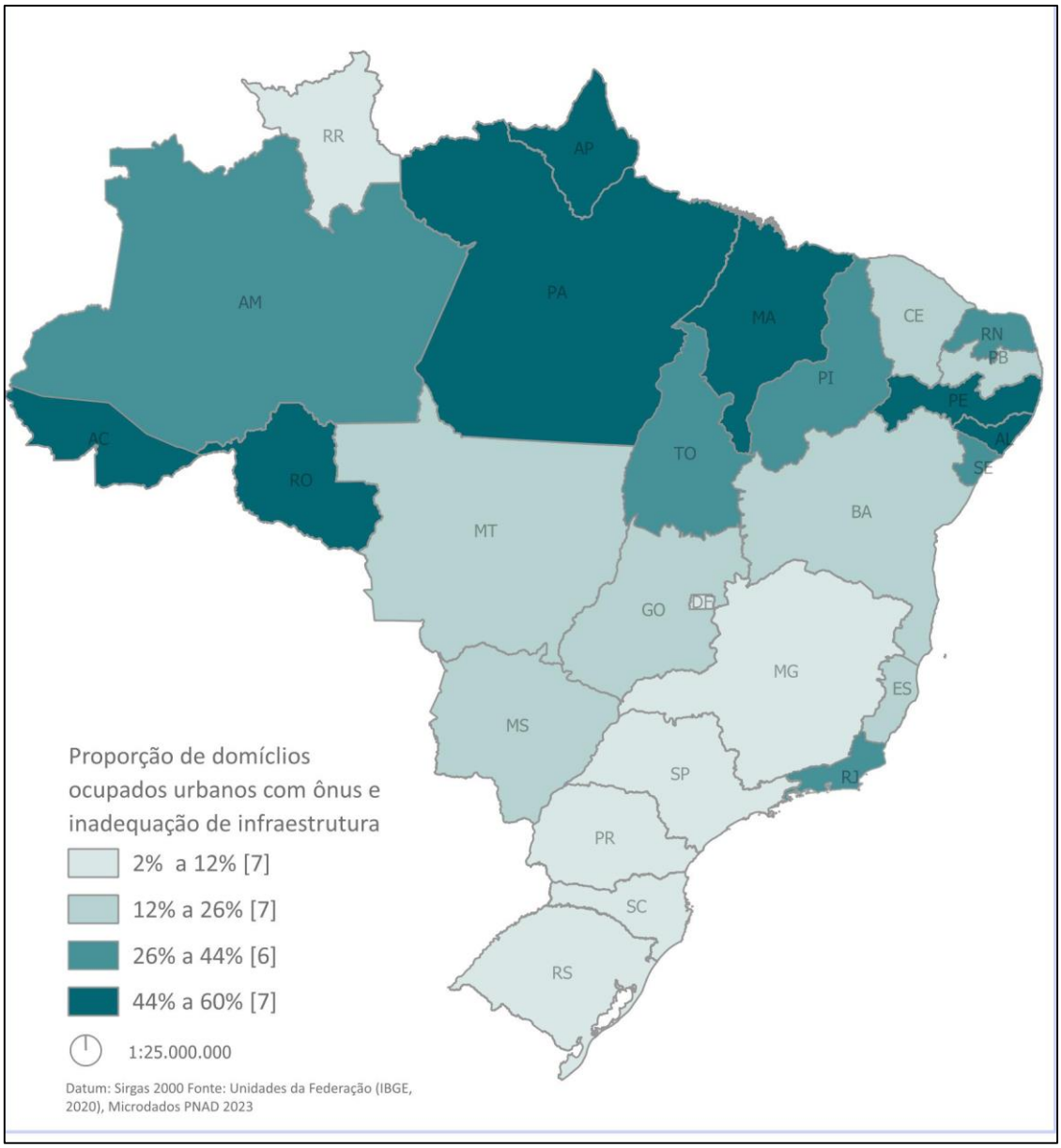

Fonte: Dados básicos: Instituto Brasileiro de Geografia e Estatística (2024).
Elaboração própria.

6.2.2 Ônus excessivo com aluguel urbano e inadequação edilícia

O Brasil possui 767.167 domicílios com sobreposição do ônus excessivo com aluguel urbano e da inadequação edilícia, o que representa 20,9% dos domicílios em ônus — ver Tabela 18. Ou seja, esses domicílios, além do ônus excessivo com o aluguel, estão acometidos pela ausência de

armazenamento de água e/ou ausência de banheiro exclusivo e/ou com todos os cômodos do domicílio servindo como dormitório e/ou com material do piso inadequado e/ou com material da cobertura inadequado. Por fim, verifica-se que os valores — absoluto e relativo — se aproximam daqueles referentes à sobreposição da inadequação de infraestrutura urbana.

Entretanto, a distribuição regional desses domicílios com ônus e inadequação edilícia se difere da distribuição do cruzamento anterior, entre ônus e inadequação de infraestrutura urbana. O Sudeste é a região com maior valor absoluto (217.515 domicílios), seguida da Nordeste (205.764 domicílios), sendo que a Sul também tem um valor expressivo (169.630 domicílios). Além do mais, é São Paulo que dispõe do maior valor quando se trata de UFs (162.422 domicílios).

O Mapa 8 ilustra as diferenças regionais referentes aos percentuais de domicílios com ônus e inadequação edilícia em relação ao total de domicílios com ônus. Nesse caso, Roraima (87,1%) e Rio Grande do Sul (61,2%) que se destacam com os maiores valores, as demais unidades da Federação não ultrapassam os 50%.

Tabela 18: Domicílios duráveis urbanos ocupados com inadequação edilícia e ônus excessivo com aluguel urbano, segundo regiões geográficas, unidades da Federação e regiões metropolitanas – Brasil – 2023

(continua)

Especificação	Domicílios com ônus		%		Total de domicílios com ônus excessivo com aluguel urbano
	Com inadequação edilícia	Sem inadequação edilícia	Com inadequação edilícia	Sem inadequação edilícia	
Norte	**83.830**	**137.070**	**37,9%**	**62,1%**	**220.900**
Rondônia	3.404	23.783	12,5%	87,5%	27.187
Acre	2.494	6.661	27,2%	72,8%	9.155
Amazonas	*20.466*	*27.616*	42,6%	57,4%	*48.082*
RM Manaus	16.436	25.286	*39,4%*	*60,6%*	41.722
Roraima	*12.540*	*1.860*	87,1%	12,9%	*14.400*
Pará	35.810	58.852	37,8%	62,2%	94.662
RM Belém	*16.910*	*18.327*	*48,0%*	*52,0%*	*35.237*
Amapá	2.601	3.150	45,2%	54,8%	5.751
RM Macapá	1.835	2.911	*38,7%*	*61,3%*	4.746
Tocantins	6.516	15.148	30,1%	69,9%	21.663
Nordeste	**205.764**	**620.518**	**24,9%**	**75,1%**	**826.282**

Especificação	Domicílios com ônus		%		Total de domicílios com ônus excessivo com aluguel urbano
	Com inadequação edilícia	Sem inadequação edilícia	Com inadequação edilícia	Sem inadequação edilícia	
Maranhão	21.261	38.632	35,5%	64,5%	59.893
RM Grande São Luís	*6.948*	*23.575*	*22,8%*	*77,2%*	*30.523*
Piauí	10.165	10.356	49,5%	50,5%	20.521
Ride Grande Teresina	*4.815*	*3.372*	*58,8%*	*41,2%*	*8.187*
Ceará	40.265	102.874	28,1%	71,9%	143.139
RM Fortaleza	*29.291*	*49.031*	*37,4%*	*62,6%*	*78.322*
Rio Grande do Norte	7.298	47.267	13,4%	86,6%	54.565
RM Natal	*6.434*	*24.652*	*20,7%*	*79,3%*	*31.086*
Paraíba	19.161	36.038	34,7%	65,3%	55.199
RM João Pessoa	*7.145*	*16.109*	*30,7%*	*69,3%*	*23.254*
Pernambuco	33.336	156.416	17,6%	82,4%	189.753
RM Recife	*21.217*	*71.131*	*23,0%*	*77,0%*	*92.347*
Alagoas	17.722	38.559	31,5%	68,5%	56.281
RM Maceió	*9.705*	*22.792*	*29,9%*	*70,1%*	*32.498*
Sergipe	17.819	25.677	41,0%	59,0%	43.496
RM Aracaju	*11.374*	*15.911*	*41,7%*	*58,3%*	*27.285*
Bahia	38.738	164.697	19,0%	81,0%	203.435
RM Salvador	*20.391*	*56.843*	*26,4%*	*73,6%*	*77.234*
Sudeste	**217.515**	**1.554.990**	**12,3%**	**87,7%**	**1.772.506**
Minas Gerais	13.745	352.608	3,8%	96,2%	366.353
RM Belo Horizonte	*5.851*	*82.635*	*6,6%*	*93,4%*	*88.486*
Espírito Santo	4.824	53.708	8,2%	91,8%	58.533
RM Grande Vitória	*3.770*	*30.296*	*11,1%*	*88,9%*	*34.066*
Rio de Janeiro	36.524	342.815	9,6%	90,4%	379.339
RM Rio de Janeiro	*27.615*	*243.660*	*10,2%*	*89,8%*	*271.275*
São Paulo	162.422	805.859	16,8%	83,2%	968.281
RM São Paulo	*72.609*	*391.662*	*15,6%*	*84,4%*	*464.271*
Sul	**169.630**	**318.754**	**34,7%**	**65,3%**	**488.383**
Paraná	44.919	144.413	23,7%	76,3%	189.332
RM Curitiba	*11.663*	*49.072*	*19,2%*	*80,8%*	*60.735*
Santa Catarina	33.859	116.714	22,5%	77,5%	150.573

Especificação	Domicílios com ônus		%		Total de domicílios com ônus excessivo com aluguel urbano
	Com inadequação edilícia	Sem inadequação edilícia	Com inadequação edilícia	Sem inadequação edilícia	
RM Florianópolis	*5.777*	*24.928*	*18,8%*	*81,2%*	*30.705*
Rio Grande do Sul	90.852	57.627	61,2%	38,8%	148.479
RM Porto Alegre	*29.154*	*20.627*	*58,6%*	*41,4%*	*49.781*
Centro-Oeste	**90.428**	**266.941**	**25,3%**	**74,7%**	**357.369**
Mato Grosso do Sul	17.953	35.765	33,4%	66,6%	53.718
Mato Grosso	15.781	58.418	21,3%	78,7%	74.198
RM Vale do Rio Cuiabá	*4.201*	*12.325*	*25,4%*	*74,6%*	*16.526*
Goiás	27.496	117.068	19,0%	81,0%	144.565
RM Goiânia	*12.693*	*51.425*	*19,8%*	*80,2%*	*64.118*
Distrito Federal	29.199	55.690	34,4%	65,6%	84.889
Brasil	**767.167**	**2.898.273**	**20,9%**	**79,1%**	**3.665.440**
Total RM	*325.834*	*1.236.569*	*20,9%*	*79,1%*	*1.562.404*
Fora das RM	*441.333*	*1.661.703*	*21,0%*	*79,0%*	*2.103.036*

Fonte: Dados básicos: Instituto Brasileiro de Geografia e Estatística (2024).

Elaboração própria.

Mapa 8: Proporção de domicílios com ônus e inadequação edilícia em relação ao total de domicílios com ônus excessivo com aluguel urbano, segundo unidades da Federação – Brasil – 2023

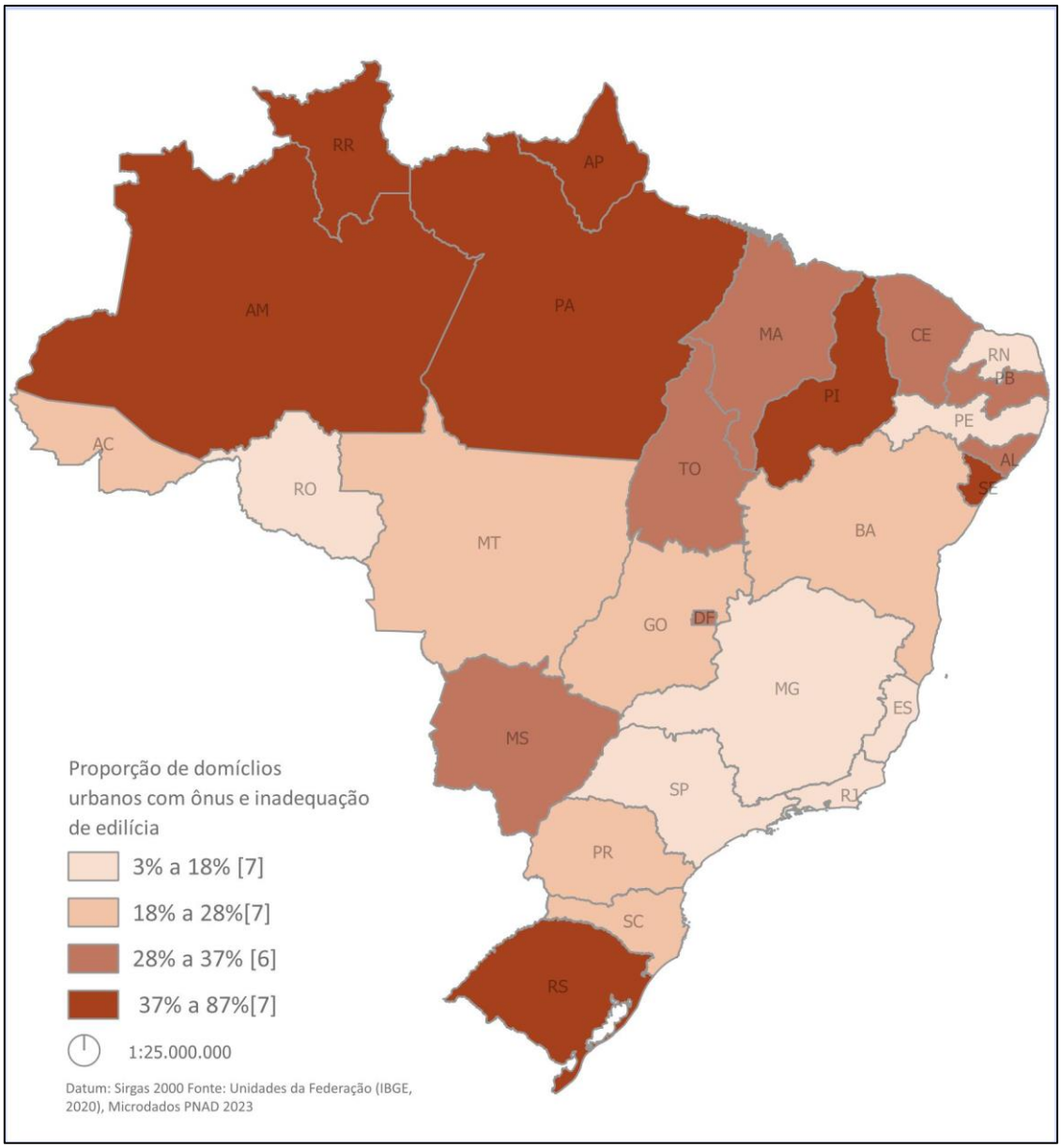

Fonte: Dados básicos: Instituto Brasileiro de Geografia e Estatística (2024).
Elaboração própria.

7 CONSIDERAÇÕES FINAIS

Este relatório apresenta as estimativas do déficit habitacional no Brasil em 2023. Primeiramente, os resultados apontam para a diversidade regional do déficit habitacional. Isso implica, portanto, na incorporação explícita das heterogeneidades espaciais para o desenvolvimento de uma política habitacional. Tal diversidade regional é também reforçada pela desagregação dos resultados do déficit habitacional pelos estratos geográficos do IBGE.

Nesse sentido, verifica-se que o déficit habitacional é predominante em domicílios de até dois salários mínimos e há o predomínio do componente ônus excessivo com o aluguel urbano no cômputo geral do indicador. Todavia, regionalmente, as habitações precárias ainda são o principal responsável pelo déficit habitacional em porções do Norte e Nordeste, além da relevância do déficit habitacional rural ser maior nessas áreas. Na porção Sudeste, Sul e Centro-Oeste, geralmente, o predomínio é do ônus excessivo com o aluguel urbano.

Mais detidamente, a partir do cruzamento do déficit habitacional com informações sobre o sexo e cor/raça do responsável, verifica-se o predomínio dos domicílios tendo mulheres como responsáveis e de pessoas pardas — exceto pela região Sul — em praticamente todos os componentes e, consequentemente, no próprio déficit habitacional.

A persistência — identificada pela pouca variação do déficit habitacional relativo — do déficit habitacional no Brasil pode estar demonstrando que a expansão do total de domicílios particulares ocupados reproduziria estruturalmente a existência de habitações em situação de déficit habitacional. Todavia, tudo indica também que esse padrão se ancora, cada vez mais, no predomínio do ônus excessivo com o aluguel, em domicílios com até dois salários mínimos de renda domiciliar, tendo uma mulher e pessoas pardas como responsáveis pelo domicílio.

Por fim, uma novidade de exposição dos dados sobre o déficit habitacional, especificamente do componente ônus excessivo com aluguel, foi o cruzamento com a identificação de alguma inadequação nesses domicílios. Os resultados indicam que a cada dez domicílios em situação de ônus excessivo com o aluguel urbano, aproximadamente quatro deles também convivem com alguma inadequação no domicílio. Além disso, regionalmente a situação é mais precária nas regiões Norte e Nordeste, especialmente no que tange a infraestrutura urbana. Em síntese, esses cruzamentos indicam mais uma dimensão do complexo problema habitacional brasileiro com a sobreposição dos problemas quantitativos e qualitativos.

REFERÊNCIAS

BENATTI, Ana Paula *et al*. Famílias monoparentais: uma revisão sistemática da literatura. **Psicologia**: ciência e profissão, Brasília, v. 41, p. 1-14, 2021. Número especial 3. Disponível em: https://www.scielo.br/j/pcp/a/msBd4PpRZXMLT7gyqWFhtVc/. Acesso em: 25 set. 2023.

BRASIL. Ministério do Desenvolvimento Social e Agrário. **Manual do entrevistador**: cadastro único para programas sociais do governo federal. 5. ed. Brasília, DF: MDSA, 2023.

FUNDAÇÃO JOÃO PINHEIRO. **A expansão das famílias unipessoais no CadÚnico e suas implicações no cálculo do déficit habitacional**. Belo Horizonte: FJP, 2023. (Nota técnica, n. 10). Disponível em: https://drive.google.com/file/d/1bxe95hus92tPkMsXO9MA5zLxk15R87WY/. Acesso em: 4 out. 2023.

FUNDAÇÃO JOÃO PINHEIRO. Centro de Estudos Políticos e Sociais. **Déficit habitacional no Brasil**: síntese. Belo Horizonte: FJP, 1995. Disponível em: http://www.bibliotecadigital.mg.gov.br/consulta/verDocumento.php?iCodigo=47940&codUsuario=0. Acesso em: 20 out. 2023.

FUNDAÇÃO JOÃO PINHEIRO. **Déficit habitacional no Brasil 2022**. Belo Horizonte: FJP, 2024. Disponível em: https://drive.google.com/file/d/13FL-MVsULmFMjkQb1nQsYzO2JVhLQvwz/. Acesso em: 1 mai. 2025.

FUNDAÇÃO JOÃO PINHEIRO. Diretoria de Estatística e Informações. **Déficit habitacional no Brasil 2015**: resultados preliminares. Belo Horizonte: FJP, 2017. (Estatística & Informações, n. 3). Disponível: http://www.bibliotecadigital.mg.gov.br/consulta/verDocumento.php?iCodigo=76867&codUsuario=0. Acesso em: 20 out. 2023.

FUNDAÇÃO JOÃO PINHEIRO. Diretoria de Estatística e Informações. **Metodologia do déficit habitacional e da inadequação de domicílios no Brasil – 2016-2019**. Belo Horizonte: FJP, 2021. Disponível em: https://fjp.mg.gov.br/wp-content/uploads/2020/12/04.03_Relatorio-Metodologia-do-Deficit-Habitacional-e-da-Inadequacao-de-Domicilios-no-Brasil-2016-2019-v-1.0_compressed.pdf. Acesso em: 20 out. 2023.

FUNDAÇÃO JOÃO PINHEIRO. Diretoria de Estatística e Informações. **Ocupações, favelas, grotas, baixadas, comunidades, ressacas, mocambos, palafitas, malocas etc**.: os desafios na mensuração da habitação precária no déficit habitacional. Belo Horizonte: FJP, 2025. (Nota técnica, n. 10). Disponível em: https://drive.google.com/file/d/1An4U3EI5CG2gBUlzBZq1Ka1taJlo4GtQ/. Acesso em: 1 maio 2025.

INSTITUTO BRASILEIRO DE GEOGRAFIA E ESTATÍSTICA. **Censo demográfico 2010**: manual do recenseador: CD-1.09. Rio de Janeiro: IBGE, 2010.

INSTITUTO BRASILEIRO DE GEOGRAFIA E ESTATÍSTICA. **Perfil dos municípios brasileiros: 2017**. Rio de Janeiro: IBGE, 2018.

INSTITUTO BRASILEIRO DE GEOGRAFIA E ESTATÍSTICA. **Pesquisa Nacional por Amostra de Domicílios Contínua**: PNAD contínua: microdados 2023. Rio de Janeiro: IBGE, 2024. Disponível em: https://www.ibge.gov.br/estatisticas/sociais/trabalho/9171-pesquisa-nacional-por-amostra-de-domicilios-continua-mensal.html?=&t=microdados. Acesso em: 21 dez. 2024.

WAJNMAN, Simone. **Demografia das famílias e dos domicílios brasileiros**. 2012. 161 f. Tese (Doutorado) – Departamento de Demografia, Faculdade de Ciências Econômicas, Universidade Federal de Minas Gerais, Belo Horizonte, 2012.

APÊNDICE A: TOTAL DE DOMICÍLIOS PARTICULARES OCUPADOS SEGUNDO REGIÕES GEOGRÁFICAS, UNIDADES FEDERATIVAS E REGIÕES METROPOLITANAS (RM) – BRASIL – 2023

Especificação	PNADC (particulares permanentes ocupados) 2023	CadÚnico (Improvisados) 2023	Total de domicílios particulares ocupados
Norte	**5.944.551**	**190.519**	**6.135.070**
Rondônia	690.026	7.305	697.331
Acre	287.921	4.694	292.615
Amazonas	1.226.956	70.830	1.297.787
RM Manaus	*837.023*	*54.738*	*891.761*
Roraima	177.578	2.127	179.705
Pará	2.737.484	76.175	2.813.659
RM Belém	*762.396*	*20.407*	*782.803*
Amapá	266.819	20.575	287.394
RM Macapá	*201.303*	*15.541*	*216.844*
Tocantins	557.765	8.814	566.579
Nordeste	**20.448.021**	**252.979**	**20.701.000**
Maranhão	2.300.068	47.339	2.347.408
RM Grande São Luís	*493.761*	*9.330*	*503.091*
Piauí	1.121.517	31.774	1.153.291
Ride[(1)] Grande Teresina	*416.442*	*1.959*	*418.401*
Ceará	3.284.128	5.650	3.289.779
RM Fortaleza	*1.429.579*	*2.026*	*1.431.605*
Rio Grande do Norte	1.254.279	19.302	*1.273.581*
RM Natal	*537.752*	*2.326*	*540.078*
Paraíba	1.469.067	25.419	1.494.486
RM João Pessoa	*471.632*	*6.599*	*478.231*
Pernambuco	3.518.963	19.804	3.538.767
RM Recife	*1.522.137*	*1.830*	*1.523.967*
Alagoas	1.160.927	24.314	1.185.242
RM Maceió	*457.144*	*5.812*	*462.956*
Sergipe	855.600	9.553	865.152
RM Aracaju	*364.551*	*3.218*	*367.769*
Bahia	5.483.472	69.823	5.553.295

Especificação	PNADC (particulares permanentes ocupados) 2023	CadÚnico (Improvisados) 2023	Total de domicílios particulares ocupados
RM Salvador	*1.568.001*	*10.620*	*1.578.621*
Sudeste	**33.679.214**	**129.970**	**33.809.184**
Minas Gerais	7.971.954	23.765	7.995.719
RM Belo Horizonte	*2.028.785*	*3.216*	*2.032.001*
Espírito Santo	1.528.462	3.023	1.531.485
RM Grande Vitória	*767.159*	*873*	*768.032*
Rio de Janeiro	6.724.926	63.720	6.788.647
RM Rio de Janeiro	*4.970.443*	*58.881*	*5.029.324*
São Paulo	17.453.872	39.462	17.493.333
RM São Paulo	*8.264.410*	*24.177*	*8.288.587*
Sul	**11.449.691**	**28.380**	**11.478.071**
Paraná	4.264.615	9.042	4.273.657
RM Curitiba	*1.371.760*	*1.905*	*1.373.665*
Santa Catarina	2.723.638	5.652	2.729.291
RM Florianópolis	*419.637*	*1.820*	*421.457*
Rio Grande do Sul	4.461.438	13.685	4.475.124
RM Porto Alegre	*1.728.963*	*3.667*	*1.732.631*
Centro-Oeste	**6.152.755**	**40.745**	**6.193.500**
Mato Grosso do Sul	1.026.671	10.145	1.036.815
Mato Grosso	1.266.262	11.945	1.278.207
RM Vale do Rio Cuiabá	*330.874*	*2.420*	*333.294*
Goiás	2.721.711	15.904	2.737.616
RM Goiânia	*1.016.475*	*3.273*	*1.019.748*
Distrito Federal	1.138.111	2.751	1.140.862
Brasil	**77.674.233**	**642.593**	**78.316.826**
Total das RM	*5.944.551*	*190.519*	*6.135.070*
Demais áreas	690.026	7.305	*697.331*

Fonte: Dados básicos: Instituto Brasileiro de Geografia e Estatística (2024); CadÚnico (2023).

Elaboração própria.

(1) Região Integrada de Desenvolvimento